# 河北省土壤类型图成果质控意见模板

| 县（市、区） | 130423 临漳县 | 提交单位 | 河北九华勘查测绘有限责任公司 |
|---|---|---|---|

## 第一部分 土壤分类

### 1、土壤图中，未按最新标准分类，运移扰动土的土属和土种一致

土壤三普土壤类型成果图

| OBJECTID_1 * | Shape * | 县名 | 三普土 | 三普亚 | 三普土属 | 三普土种 |
|---|---|---|---|---|---|---|
| 222 | 面 | 临漳 | 褐土 | 潮褐土 | 泥砂质潮褐土 | 均砂壤泥砂质潮 |
| 223 | 面 | 临漳 | 褐土 | 潮褐土 | 泥砂质潮褐土 | 均砂壤泥砂质潮 |
| 224 | 面 | 临漳 | 褐土 | 潮褐土 | 泥砂质潮褐土 | 均砂壤泥砂质潮 |
| 225 | 面 | 临漳 | 褐土 | 潮褐土 | 泥砂质潮褐土 | 均砂壤泥砂质潮 |
| 226 | 面 | 临漳 | 褐土 | 潮褐土 | 泥砂质潮褐土 | 均砂质泥砂质潮 |
| 227 | 面 | 临漳 | 褐土 | 潮褐土 | 泥砂质潮褐土 | 均砂质泥砂质潮 |
| 228 | 面 | 临漳 | 褐土 | 潮褐土 | 泥砂质潮褐土 | 均砂质泥砂质潮 |
| 229 | 面 | 临漳 | 褐土 | 潮褐土 | 泥砂质潮褐土 | 均砂质泥砂质潮 |
| 230 | 面 | 临漳 | 褐土 | 潮褐土 | 泥砂质潮褐土 | 均砂质泥砂质潮 |
| 231 | 面 | 临漳 | 褐土 | 潮褐土 | 泥砂质潮褐土 | 均砂质泥砂质潮 |
| 232 | 面 | 临漳 | 褐土 | 潮褐土 | 泥砂质潮褐土 | 均砂质泥砂质潮 |
| 233 | 面 | 临漳 | 褐土 | 潮褐土 | 泥砂质潮褐土 | 黏壤底砂泥砂质 |
| 234 | 面 | 临漳 | 褐土 | 潮褐土 | 泥砂质潮褐土 | 黏壤底砂泥砂质 |
| 235 | 面 | 临漳 | 褐土 | 潮褐土 | 泥砂质潮褐土 | 黏壤底砂泥砂质 |
| 236 | 面 | 临漳 | 褐土 | 潮褐土 | 泥砂质潮褐土 | 黏壤底砂泥砂质 |
| 237 | 面 | 临漳 | 褐土 | 潮褐土 | 泥砂质潮褐土 | 黏壤底砂泥砂质 |
| 238 | 面 | 临漳 | 褐土 | 潮褐土 | 泥砂质潮褐土 | 黏壤体砂泥砂质 |
| 239 | 面 | 临漳 | 褐土 | 潮褐土 | 泥砂质潮褐土 | 黏壤体砂泥砂质 |
| 240 | 面 | 临漳 | 褐土 | 潮褐土 | 泥砂质潮褐土 | 壤体砂泥砂质潮 |
| 241 | 面 | 临漳 | 褐土 | 潮褐土 | 泥砂质潮褐土 | 壤体砂泥砂质潮 |
| 242 | 面 | 临漳 | 人工土 | 扰动土 | 运移扰动土 | <空> |
| 243 | 面 | 临漳 | 人工土 | 扰动土 | 运移扰动土 | <空> |
| 244 | 面 | 临漳 | 褐土 | 潮褐土 | 泥砂质潮褐土 | 壤底砂泥砂质潮 |
| 245 | 面 | 临漳 | 潮土 | 典型潮土 | 壤质石灰性潮土 | 均壤质石灰性潮 |

| | | | |
|---|---|---|---|
| 人工土 | 扰动土 | 运移扰动土 | 运移扰动土 |
| 人工土 | 填充土 | 工矿填充土 | 工矿填充土 |

### 2、土壤图中，该命名不存在于最新分类标准中

土壤三普土壤类型成果图

| OBJECTID_1 * | Shape * | 县名 | 三普土 | 三普亚 | 三普土属 | 三普土种 | Sh |
|---|---|---|---|---|---|---|---|
| 1 | 面 | 临漳 | 潮土 | 典型潮土 | 黏质石灰性潮土 | 黏底砂石灰性潮土 | |
| 2 | 面 | 临漳 | 潮土 | 典型潮土 | 壤质潮土 | 均壤质潮土 | |
| 4 | 面 | 临漳 | 潮土 | 典型潮土 | 壤质潮土 | 壤体砂潮土 | |
| 9 | 面 | 临漳 | 潮土 | 典型潮土 | 壤质石灰性潮土 | 黏壤夹砂石灰性潮 | |
| 22 | 面 | 临漳 | 潮土 | 典型潮土 | 砂质石灰性潮土 | 砂底黏石灰性潮土 | |
| 23 | 面 | 临漳 | 潮土 | 典型潮土 | 砂质石灰性潮土 | 砂底壤石灰性潮土 | |
| 24 | 面 | 临漳 | 潮土 | 典型潮土 | 砂质石灰性潮土 | 砂壤夹黏石灰性潮 | |
| 25 | 面 | 临漳 | 潮土 | 典型潮土 | 砂质石灰性潮土 | 砂壤体黏石灰性潮 | |
| 26 | 面 | 临漳 | 潮土 | 湿潮土 | 壤质湿潮土 | 均壤质湿潮土 | |

## 3、表层样点有大规模土属土种命名和最新标准对不上

类型与分类清单检查：共发现 535 个问题

1：省级分类清单无该土属

2：省级分类清单无该土属

3：省级分类清单无该土属

4：省级分类清单无该土种

5：省级分类清单无该土属

6：省级分类清单无该土属

土壤三普表层样点

| ZLDWDM | ZLDWMC | SB | TL | YL | TS | TZ | YDLX |
|---|---|---|---|---|---|---|---|
| 1304231020480000000 | 刘家村 | HBa_5_240 | 潮土 | 典型潮 | 石灰性潮壤土 | 轻壤质石灰性潮土 | 表层样 |
| 1304231040010000000 | 称西村 | HBa_5_87 | 潮土 | 典型潮 | 石灰性潮壤土 | 中壤质石灰性潮土 | 表层样 |
| 1304232010530000000 | 潘家村 | HBa_3_69 | 潮土 | 典型潮 | 潮黏土 | 黏质底砂潮土 | 表层样 |
| 1304232020030000000 | 西羊羔南 | CBd_2_145 | 褐土 | 潮褐土 | 泥砂质潮褐土 | 轻壤质身砂泥砂质 | 表层样 |
| 1304232000150000000 | 双庙 | HBa_5_218 | 潮土 | 典型潮 | 石灰性潮壤土 | 轻壤质底黏石灰性 | 表层样 |
| 1304231020330000000 | 陈小庄 | HBa_5_210 | 潮土 | 典型潮 | 石灰性潮壤土 | 轻壤质底砂石灰性 | 表层样 |
| 1304232040230000000 | 梅庄村 | HBa_5_162 | 潮土 | 典型潮 | 石灰性潮壤土 | 砂壤质石灰性潮土 | 表层样 |
| 1304232060140000000 | 浴安台 | HBa_5_240 | 潮土 | 典型潮 | 石灰性潮壤土 | 轻壤质石灰性潮土 | 表层样 |
| 1304231010180000000 | 北头村 | HBa_5_87 | 潮土 | 典型潮 | 石灰性潮壤土 | 中壤质石灰性潮土 | 表层样 |
| 1304232040260000000 | 东葛庄村 | HBa_5_162 | 潮土 | 典型潮 | 石灰性潮壤土 | 砂壤质石灰性潮土 | 表层样 |
| 1304232000020000000 | 前野郭村 | HBe_10_142 | 潮土 | 盐化潮 | 氯化物盐化潮土 | 轻壤质轻度氯化物 | 表层样 |
| 1304232070260000000 | 羊羔屯 | GEc_10_4 | 风沙 | 草甸风 | 草甸风沙土 | 草甸风沙土 | 表层样 |
| 1304232010070000000 | 董村 | HBa_5_247 | 潮土 | 典型潮 | 石灰性潮壤土 | 轻壤质身黏石灰性 | 表层样 |
| 1304231030230000000 | 涉县庄 | HBa_5_59 | 潮土 | 典型潮 | 石灰性潮壤土 | 中壤质夹砂石灰性 | 表层样 |
| 1304232010270000000 | 花王村 | HBa_5_87 | 潮土 | 典型潮 | 石灰性潮壤土 | 中壤质石灰性潮土 | 表层样 |
| 1304232070030000000 | 前屯 | HBa_5_162 | 潮土 | 典型潮 | 石灰性潮壤土 | 砂壤质石灰性潮土 | 表层样 |
| 1304232060250000000 | 贺北村 | JAd_1_65 | 沼泽 | 草甸沼 | 草甸沼泽土 | 轻壤质草甸沼泽土 | 表层样 |
| 1304231020410000000 | 孟村铺村 | HBa_5_87 | 潮土 | 典型潮 | 石灰性潮壤土 | 中壤质石灰性潮土 | 表层样 |
| 1304231050140000000 | 显王村 | HBa_5_244 | 潮土 | 典型潮 | 石灰性潮壤土 | 轻壤质身砂石灰性 | 表层样 |
| 1304231020500000000 | 郭村 | HBa_5_240 | 潮土 | 典型潮 | 石灰性潮壤土 | 轻壤质石灰性潮土 | 表层样 |
| 1304231000390000000 | 西北角2 | CBd_2_132 | 褐土 | 潮褐土 | 泥砂质潮褐土 | 轻壤质底砂泥砂质 | 表层样 |
| 1304231030240000000 | 东南王 | GEc_10_4 | 风沙 | 草甸风 | 草甸风沙土 | 草甸风沙土 | 表层样 |
| 1304232000010000000 | 西狄邱村 | HBa_5_218 | 潮土 | 典型潮 | 石灰性潮壤土 | 轻壤质底黏石灰性 | 表层样 |

## 4、报告中部分土种命名和最新版本对不上

| 土类 | 亚类 | 土属 | 土种 | 面积 |
|---|---|---|---|---|
| | | | 均砂质潮土 | 39203 |
| | | 砂质石灰性潮土 | 均砂壤石灰性潮土 | 154843 |
| | | | 均砂质石灰性潮土 | 16643 |
| | | | 砂底黏石灰性潮土 | 4522 |
| | | | 砂底壤石灰性潮土 | 273 |
| | | | 砂壤夹黏石灰性潮土 | 4944 |
| | | | 砂壤体黏石灰性潮土 | 517 |
| | 湿潮土 | 壤质湿潮土 | 均壤质湿潮土 | 3684 |
| | | | 均黏壤泥砂质潮褐土 | 7568 |
| | | | 均壤质泥砂质潮褐土 | 126346 |
| | | | 均砂壤泥砂质潮褐土 | 56223 |
| | | | 均砂质泥砂质潮褐土 | 20983 |

# 第二部分 制图过程

## 1、遥感影像数据和二普土壤图偏差较大

## 2、未明确说明选取的虚点对土壤类型代表性的证明示例，无法确定虚点选取了典型位置

钙含量、pH、质地类型、盐分、碱化度等指标数据）、剖面样点数据，作为三普表层和剖面样点虚点。

（2）参考二普土壤类型纸质图，图上所有二普剖面样点数据作为二普剖面虚点。

（3）组织专业调查专家进行野外实地踏勘，观察土壤剖面特征、土壤质地、结构等。将野外踏勘取样点作为外业虚点。

（4）参考土壤类型图编制规范，利用二普土壤图、高分遥感影像和高程、坡度、母质等关键成土因素，结合专家经验知识，根据景观特征、地形部位等因素的相近或相似性判断各土种易形成的区域，提取典型虚点。

临漳县共提取虚点 2152 个，其中二普剖面虚点 44 个，三普剖面虚点 18 个，三普表层样虚点 535 个，野外踏勘外业虚点 122 个，结合专家经验成土因素提取的典型虚点 1433 个。见下图：

## 3、没有在推测制图部分突出制图效果最优最劣的的情况

**4.6.3 推测制图成果分析**

在多次预测与对比中发现，临漳县土种数量多达 38 个，多次土种预测结果精度很低，总体精度在 25%-27%之间，Kappa 系数低于 0.5，经过多次调整样点与环境变量，推测制图精度虽然达到了合格水平，但距离边界应用仍有一定差距。

最终推测制图成果模型总体精度为 28.32%（每 100 个土壤样本中约有 28 个被正确分类），Kappa 系数为 0.412（模型比随机猜测准确 41.2%，但存在显著误差，0.4-0.6 为合格，＞0.6 为良好）。

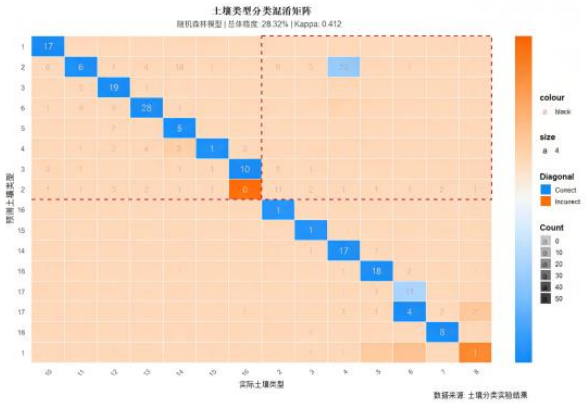


图 4-40 土壤类型分类混淆矩阵

59

通过将推测成果与校核成果对比发现，推测制图的土种分布"褐土、潮土、人工土"的分布规律基本正确，然而从边界上存在接线粗犷，可信度不高。

通过多方面原因分析，导致推测制图可信度不高的原因可能有以下几方面：

其一，临漳县土壤以潮土为主，成土母质为冲积物，成土过程以潴育化、潮

# 第三部分 制图结果

## 1、各数据使用的都不是投影坐标系，需进行投影转换

| | |
|---|---|
| 地理坐标系: | GCS_China_Geodetic_Coordinate_System_2000 |
| 基准面: | D_China_2000 |
| 本初子午线: | Greenwich |
| 角度单位: | Degree |

## 2、各矢量数据字段空值常见

可能改变区

| OBJECTID * | Shape * | 代号 | 二普土类 | 二普亚类 | 二普土属 | 二普土种 | 面积 | Shape_Length | Shape_Area | 改变类型 |
|---|---|---|---|---|---|---|---|---|---|---|
| 1 | 面 | G3-00 | 沼泽土 | 草甸沼泽 | 壤质草甸沼 | 轻壤质草甸沼 | 6.49 | 0.011243 | 0.000007 | 就源 |
| 2 | 面 | G3-00 | 沼泽土 | 草甸沼泽 | 壤质草甸沼 | 轻壤质草甸沼 | 15.86 | 0.017555 | 0.000016 | 就源 |
| 3 | 面 | G3-00 | 沼泽土 | 草甸沼泽 | 壤质草甸沼 | 轻壤质草甸沼 | 13.34 | 0.01494 | 0.000013 | 就源 |
| 4 | 面 | G3-00 | 沼泽土 | 草甸沼泽 | 壤质草甸沼 | 轻壤质草甸沼 | 8.5 | 0.011075 | 0.000009 | 就源 |
| 5 | 面 | G3-00 | 沼泽土 | 草甸沼泽 | 壤质草甸沼 | 轻壤质草甸沼 | 245.62 | 0.06345 | 0.000246 | 就源 |
| 6 | 面 | GL3-31 | 潮土 | 沼泽化潮 | 砂质潮土 | 轻壤质砂沙盐 | 46.45 | 0.045541 | 0.000047 | 就源 |
| 7 | 面 | G3-00 | 沼泽土 | 草甸沼泽 | 壤质草甸沼 | 轻壤质草甸沼 | 6.87 | 0.009648 | 0.000007 | 就源 |
| 8 | 面 | <空> | <空> | <空> | <空> | <空> | 17.047069 | 0.035422 | 0.000017 | 新增斑地 |
| 9 | 面 | <空> | <空> | <空> | <空> | <空> | 5.274596 | 0.015648 | 0.000005 | 新增斑地 |
| 10 | 面 | <空> | <空> | <空> | <空> | <空> | 8.07108 | 0.016863 | 0.000008 | 新增斑地 |
| 11 | 面 | <空> | <空> | <空> | <空> | <空> | 10.73004 | 0.01758 | 0.000011 | 新增斑地 |
| 12 | 面 | <空> | <空> | <空> | <空> | <空> | 6.49029 | 0.020313 | 0.000007 | 新增斑地 |
| 13 | 面 | <空> | <空> | <空> | <空> | <空> | 17.605982 | 0.047966 | 0.000018 | 新增斑地 |
| 14 | 面 | <空> | <空> | <空> | <空> | <空> | 11.434702 | 0.014952 | 0.000011 | 新增斑地 |
| 15 | 面 | <空> | <空> | <空> | <空> | <空> | 3.378742 | 0.017444 | 0.000003 | 新增斑地 |
| 16 | 面 | <空> | <空> | <空> | <空> | <空> | 3.676699 | 0.00876 | 0.000004 | 新增斑地 |
| 17 | 面 | <空> | <空> | <空> | <空> | <空> | 7.326478 | 0.013691 | 0.000007 | 新增斑地 |
| 18 | 面 | <空> | <空> | <空> | <空> | <空> | 3.999143 | 0.013508 | 0.000004 | 新增斑地 |
| 19 | 面 | <空> | <空> | <空> | <空> | <空> | 4.036611 | 0.012545 | 0.000004 | 新增斑地 |
| 20 | 面 | <空> | <空> | <空> | <空> | <空> | 6.256354 | 0.013574 | 0.000006 | 新增斑地 |
| 21 | 面 | <空> | <空> | <空> | <空> | <空> | 3.874878 | 0.017083 | 0.000004 | 新增斑地 |
| 22 | 面 | <空> | <空> | <空> | <空> | <空> | 11.796041 | 0.01771 | 0.000012 | 新增斑地 |
| 23 | 面 | <空> | <空> | <空> | <空> | <空> | 5.525632 | 0.01722 | 0.000006 | 新增斑地 |
| 24 | 面 | <空> | <空> | <空> | <空> | <空> | 5.123096 | 0.026427 | 0.000005 | 新增斑地 |
| 25 | 面 | <空> | <空> | <空> | <空> | <空> | 3.747301 | 0.01149 | 0.000004 | 新增斑地 |
| 26 | 面 | <空> | <空> | <空> | <空> | <空> | 4.643412 | 0.013173 | 0.000005 | 新增斑地 |
| 27 | 面 | <空> | <空> | <空> | <空> | <空> | 4.269781 | 0.017203 | 0.000004 | 新增斑地 |
| 28 | 面 | <空> | <空> | <空> | <空> | <空> | 4.529016 | 0.015361 | 0.000005 | 新增斑地 |
| 29 | 面 | <空> | <空> | <空> | <空> | <空> | 19.754152 | 0.019247 | 0.00002 | 新增斑地 |
| 30 | 面 | <空> | <空> | <空> | <空> | <空> | 3.562458 | 0.012713 | 0.000004 | 新增斑地 |
| 31 | 面 | <空> | <空> | <空> | <空> | <空> | 4.283752 | 0.019329 | 0.000004 | 新增斑地 |
| 32 | 面 | <空> | <空> | <空> | <空> | <空> | 3.426853 | 0.009872 | 0.000003 | 新增斑地 |
| 33 | 面 | <空> | <空> | <空> | <空> | <空> | 3.555675 | 0.01157 | 0.000004 | 新增斑地 |
| 34 | 面 | <空> | <空> | <空> | <空> | <空> | 6.159191 | 0.017159 | 0.000006 | 新增斑地 |
| 35 | 面 | <空> | <空> | <空> | <空> | <空> | 3.70559 | 0.013175 | 0.000004 | 新增斑地 |

(0 / 211 已选择)

表

土壤三普表层样点

| JD | WD | XJXZQDM | nvs | slope | tmb7 | twi | kdx | TRZD | PH | SRXYZL | OM |
|---|---|---|---|---|---|---|---|---|---|---|---|
| 114.48915 | 36.369873 | | 0 | 0 | 0 | 0 | 0 | 黏壤土 | 8.29 | 0.695 | 24.8 |
| 114.64589 | 36.268741 | | 0 | 0 | 0 | 0 | 0 | <空> | <空> | 0.757 | <空> |
| 114.660109 | 36.265411 | | 0 | 0 | 0 | 0 | 0 | <空> | <空> | 0.592 | <空> |
| 114.657651 | 36.257838 | | 0 | 0 | 0 | 0 | 0 | <空> | <空> | 0.623 | <空> |
| 114.678644 | 36.329196 | | 0 | 0 | 0 | 0 | 0 | 砂质黏壤土 | 8.19 | 0.630 | 17.0 |
| 114.690917 | 36.331287 | | 0 | 0 | 0 | 0 | 0 | <空> | 8.23 | 0.607 | 15.4 |
| 114.704414 | 36.327617 | | 0 | 0 | 0 | 0 | 0 | 壤质黏土 | 8.25 | 0.405 | 14.7 |
| 114.712524 | 36.327786 | | 0 | 0 | 0 | 0 | 0 | <空> | 8.38 | 0.571 | 15.9 |
| 114.717462 | 36.322008 | | 0 | 0 | 0 | 0 | 0 | 砂质壤土 | 8.47 | 0.332 | 8.12 |
| 114.75284 | 36.308408 | | 0 | 0 | 0 | 0 | 0 | <空> | 8.28 | 0.635 | 18.9 |
| 114.746214 | 36.304591 | | 0 | 0 | 0 | 0 | 0 | 粉(砂)质壤 | 8.13 | 0.781 | 19.4 |
| 114.75584 | 36.310507 | | 0 | 0 | 0 | 0 | 0 | <空> | 8.31 | 0.518 | 16.1 |
| 114.671522 | 36.160506 | | 0 | 0 | 0 | 0 | 0 | 粉(砂)质黏 | 8.38 | 0.685 | 19.2 |
| 114.680761 | 36.153103 | | 0 | 0 | 0 | 0 | 0 | <空> | <空> | 0.482 | <空> |
| 114.682809 | 36.145106 | | 0 | 0 | 0 | 0 | 0 | <空> | <空> | 0.446 | <空> |
| 114.423786 | 36.332186 | | 0 | 0 | 0 | 0 | 0 | <空> | 8.20 | 0.638 | 15.6 |
| 114.423451 | 36.327437 | | 0 | 0 | 0 | 0 | 0 | 黏壤土 | 8.21 | 0.673 | 21.4 |
| 114.669755 | 36.218832 | | 0 | 0 | 0 | 0 | 0 | <空> | <空> | 0.628 | <空> |
| 114.668334 | 36.215044 | | 0 | 0 | 0 | 0 | 0 | <空> | <空> | 0.524 | <空> |
| 114.660962 | 36.324545 | | 0 | 0 | 0 | 0 | 0 | <空> | 8.40 | 0.384 | 8.32 |
| 114.447305 | 36.318792 | | 0 | 0 | 0 | 0 | 0 | 黏壤土 | 8.08 | 0.905 | 24.6 |
| 114.447078 | 36.316873 | | 0 | 0 | 0 | 0 | 0 | <空> | 7.99 | 0.625 | 18.4 |
| 114.471218 | 36.320042 | | 0 | 0 | 0 | 0 | 0 | <空> | <空> | 0.560 | <空> |
| 114.470519 | 36.310886 | | 0 | 0 | 0 | 0 | 0 | <空> | <空> | 0.627 | <空> |
| 114.692452 | 36.225946 | | 0 | 0 | 0 | 0 | 0 | <空> | <空> | 0.463 | <空> |
| 114.704166 | 36.224504 | | 0 | 0 | 0 | 0 | 0 | <空> | <空> | 0.548 | <空> |
| 114.489788 | 36.401967 | | 0 | 0 | 0 | 0 | 0 | 砂质壤土 | 8.35 | 0.585 | 18.3 |
| 114.638075 | 36.294125 | | 0 | 0 | 0 | 0 | 0 | <空> | 8.07 | 0.598 | 15.7 |
| 114.648175 | 36.299022 | | 0 | 0 | 0 | 0 | 0 | 壤质黏土 | 8.22 | 0.425 | 17.8 |
| 114.649515 | 36.286697 | | 0 | 0 | 0 | 0 | 0 | <空> | 8.18 | 0.604 | 26.3 |

1 (0 / 535 已选择)

土壤三普表层样点

## 3、存在大量拓扑问题

空间拓扑检查

检查完成

**几何有效性检查：共检查219个图斑，发现1个问题**

1. 图斑ID75：空间自相交，关键点的空间坐标是[114.666149823 36.260769506]

**碎屑多边形检查：共检查219个图斑，发现219个问题**

2. 图斑ID1面积过小（碎屑多边形），面积: 0.00 平方米
3. 图斑ID2面积过小（碎屑多边形），面积: 0.00 平方米
4. 图斑ID4面积过小（碎屑多边形），面积: 0.00 平方米
5. 图斑ID9面积过小（碎屑多边形），面积: 0.00 平方米

## 4、表层样点的土属土种和土壤图的土属土种有对不上

与[illegible]类型检查：共发现 535 个问题

图斑 90：土属不一致

图斑 121：土属不一致

图斑 75：土属不一致

图斑 214：土种不一致

图斑 123：土属不一致

图斑 126：土属不一致

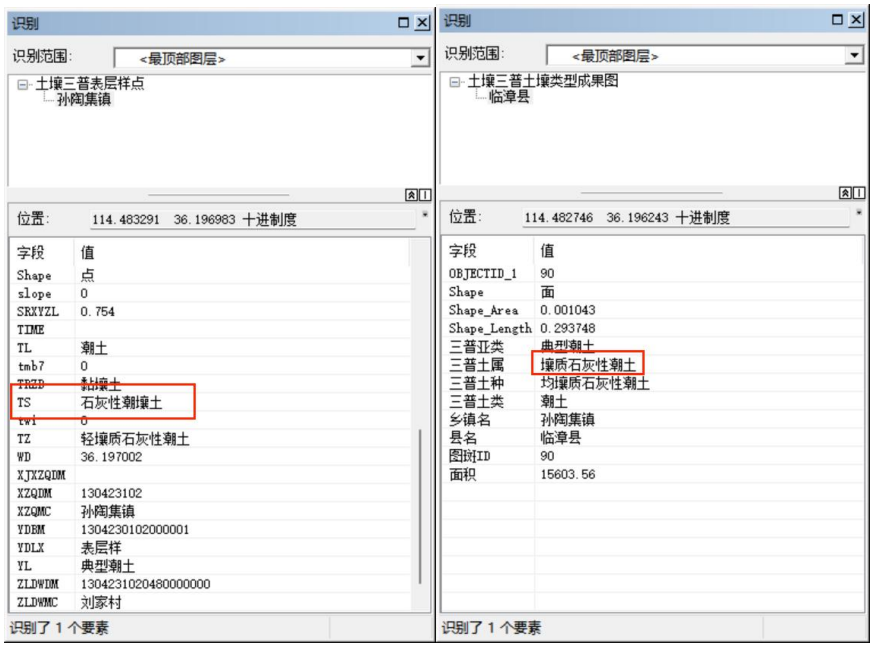


## 5、剖面样点的土属土种和土壤图的土属土种有对不上

1. 上图类型与剖面类型检查：共发现 20 个问题
2. 剖面 1 vs 图斑 84：土属不一致
3. 剖面 2 vs 图斑 175：土属不一致
4. 剖面 3 vs 图斑 83：土类不一致
5. 剖面 4 vs 图斑 26：土类不一致
6. 剖面 5 vs 图斑 96：土属不一致
7. 剖面 6 vs 图斑 86：土属不一致

### 6、潮土处坡度过大，需核查

### 7、请根据数据库规范，仔细检查各个过程、成果数据的属性表是否包含所需字段、字段命名是否规范、字段类型是否符合要求、字段内容是否被截断

## 第四部分 图面表达

### 1、指北针太小，且放的位置不合适

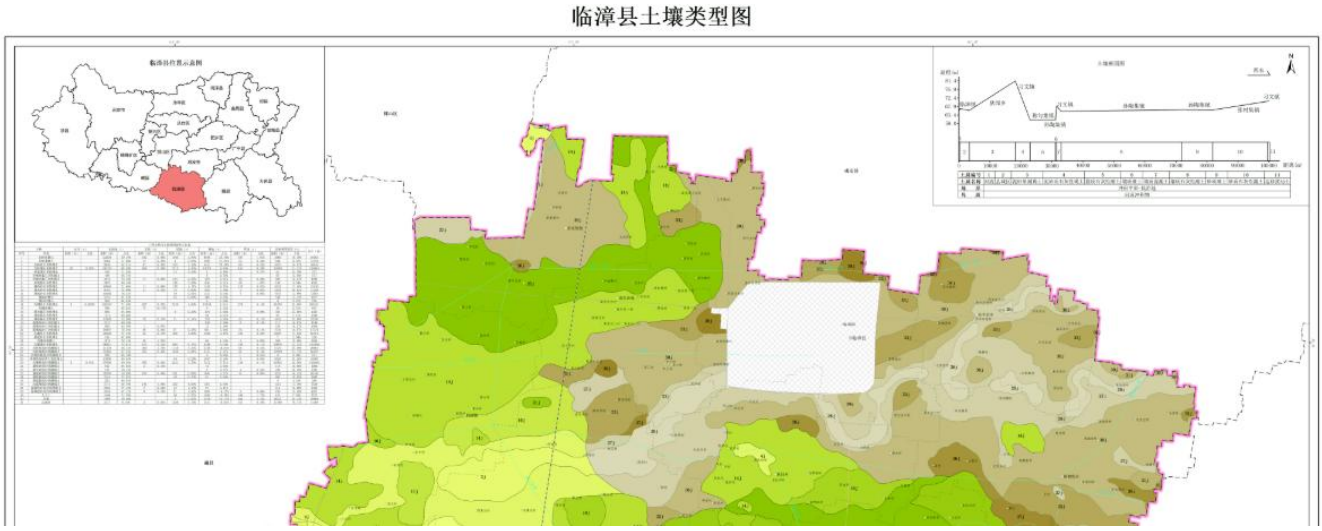

## 2、居民点选取的上图颜色不符合规范

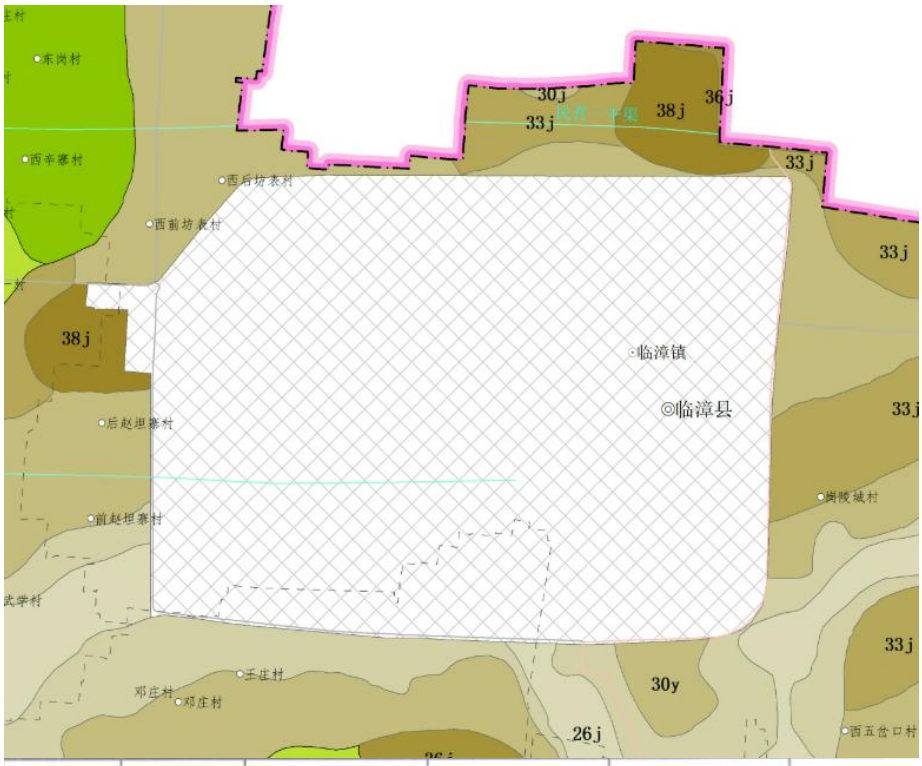


| 地类编码 | 地类名称 | 编码式样 | 符号式样 | RGB | CMYK |
|---|---|---|---|---|---|
| 201 | 城市 | 201 | 4.0(3.0) | R218 G37 B29<br>R229 G103 B102 | C0 M100 Y100 K0<br>C0 M70 Y50 K0 |
| 202 | 建制镇 | 202 | 2.0(1.5) | R218 G37 B29<br>R229 G103 B102 | C0 M100 Y100 K0<br>C0 M70 Y50 K0 |

## 3、断面图没有标注土种

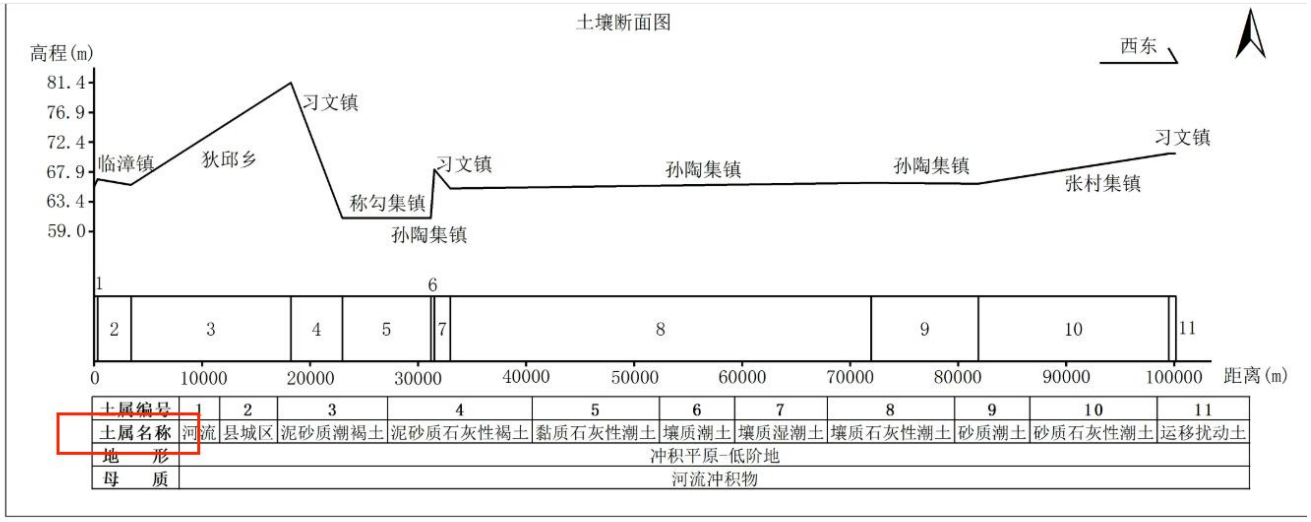


| 土属编号 | 1 | 2 | 3 | 4 | 5 | 6 | 7 | 8 | 9 | 10 | 11 |
|---|---|---|---|---|---|---|---|---|---|---|---|
| 土属名称 | 河流 | 县城区 | 泥砂质潮褐土 | 泥砂质石灰性褐土 | 黏质石灰性潮土 | 壤质潮土 | 壤质湿潮土 | 壤质石灰性潮土 | 砂质潮土 | 砂质石灰性潮土 | 运移扰动土 |
| 地　形 | 冲积平原-低阶地 | | | | | | | | | | |
| 母　质 | 河流冲积物 | | | | | | | | | | |

## 4、土壤图缺少等高线

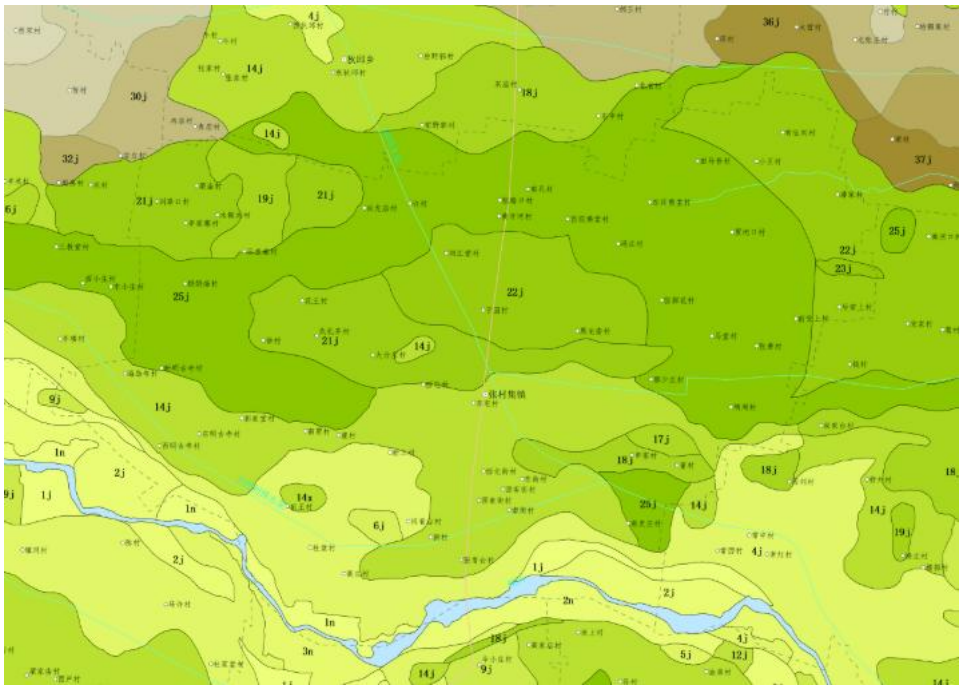

## 5、部分公路、水系等重要地物没有标注

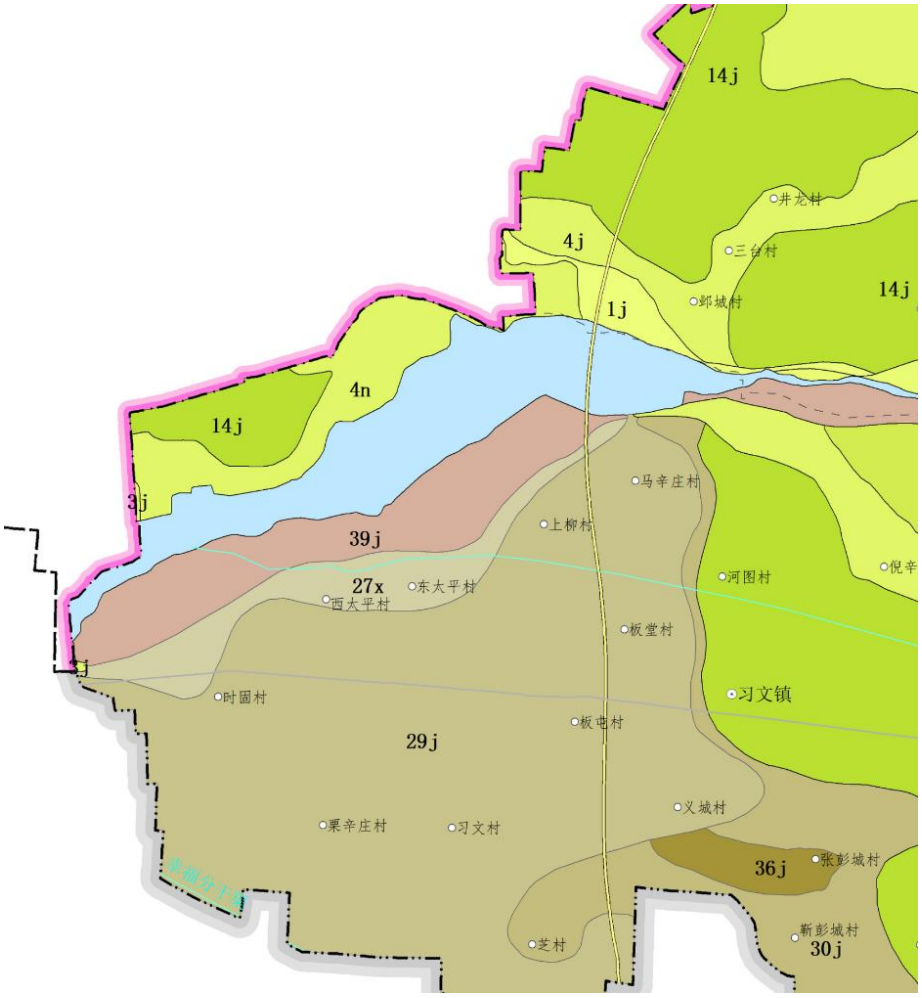

# 第五部分 报告质量

## 1、技术报告、工作报告无图目录与表目录

## 2、技术报告、工作报告中，标题字体大小错误，标题编号层级使用错误，行距错误，需核查

第一章 概述

1.1 地理位置

临漳县位于河北省最南端，介于东经 114°20′-114°46′，北纬 36°7′-36°24′之间，地处中原腹地，处于太行山东麓，晋冀鲁豫四省交界处，东邻魏县，西接磁县，北达成安县，南连河南省安阳县，东西长 35 千米，南北宽 26.5 千米，县域总面积约 741.78 平方公里。见下图。

## 3、技术报告中，规范的（试行版）在书名号里面

2.1.2 土壤分类系统

根据土壤二普成果以及临漳县土壤历史资料，结合《GB/T 17296-2009 中国土壤分类与代码》和《第三次全国土壤普查土壤分类系统》（试行版）规范，按照土壤土类、亚类、土属、土种的分类系统，临漳县校核成果有 4 个土类、 7 个亚类、12 个土属、44 个土种。潮土分为典型潮土、湿潮土与盐化潮土 3 个亚

## 4、技术报告和工作报告中的虚点数量对不上

壤图上拾取土壤类型典型点（虚点，非实际调查观测点）作为补充性样本点。临漳县共提取虚点 2150 个，其中二普剖面虚点 252 个，三普剖面虚点 20 个，三普表层样虚点 535 个，野外踏勘外业虚点 92 个，结合专家经验成土因素提取的典型虚点 1251 个。

临漳县共提取虚点 2152 个，其中二普剖面虚点 44 个，三普剖面虚点 18 个，三普表层样虚点 535 个，野外踏勘外业虚点 122 个，结合专家经验成土因素提取的典型虚点 1433 个。见下图：

## 5、工作报告中以亩为单位的没有保留整数

分：1：25000、1：50000、1：10000 地形图图式》（见图 2-2）编制 1：5 万临漳县三普土壤类型分布图(jpg 格式，DPI 大于 300)，最小上图控制在图上 0.5cm²，实地面积 12.5hm²（187.5 亩），注意具体执行中要考虑区域土壤景观实际灵活处理。

## 6、确认工作报告提交的是否为最终版本

| | | | | | | |
|---|---|---|---|---|---|---|
| 7 | 赵梦月 | 女 | 助工 | 计算机专业 | 内业技术员 | |
| 8 | 王志远 | 女 | 助工 | 工程测量 | 外业技术员 | |

3.专家技术指导组

为保证项目的顺利实施，我单位邀请市局土肥站、县局土肥站、省农科院专家组建技术指导团队，为项目实施提供专业技术支撑。

临漳县专家组主要人员见下表。

记不住我的名字
插入市局县局土肥站人名

表 2-2 临漳县主要人员构成

| 序号 | 姓名 | 性别 | 职务或职称 | 备注 |
|---|---|---|---|---|
| 1 | 赵明亮 | 男 | 市土肥站站长 | |
| 2 | 司峻宇 | 男 | 市土肥站副站长 | |
| 3 | 毛卫东 | 男 | 市土肥站副站长 | |
| 4 | 庞分泉 | 男 | 县土肥站站长 | |
| 5 | 茹淑华 | 女 | 研究员 | 河北省农科院土壤学专家 |
| 6 | 贾树龙 | 男 | 研究员 | 河北省农科院土壤学专家 |

（三）人员培训

记不住我的名字
（三）人员培训（省市县技术单位技
如有考核需写考核情况）

1.省级培训

2024 年 8 月 2 日，我单位在石家庄市参加了河北省三普办组织的河北省第三次土壤普查成果编制技术培训班（第二期）。

## 7、报告中数字附近常带有空格

### 1.2.3 气候条件

临漳县属于暖温带半湿润大陆性季风气候，四季分明，光照充足，热量丰富，降水集中但分布不均。根据临漳县气象局近 30 年的气候资料统计，县域内年平均气温为 13.5℃，最冷月（1 月）平均气温为- 2.3℃，最热月（7 月）平均气温为 26.9℃，无霜期平均为 203 天，年平均日照时数为 2557 小时，年平均太阳总辐射量为 121.5 千卡/平方厘米，能够满足农作物一年两熟的生长需求。

降水方面，临漳县年平均降水量为 556.2 毫米，但降水季节分布不均，夏季（6-8 月）降水量占全年总降水量的 65% 以上，且多以暴雨形式出现，容易引

# 第六部分 其他

## 1、PROCESS 数据集中缺少推测的土壤三普图、不确定性分布图、土壤二普土壤图室内校核前图斑、土壤二普土壤图室内校核后图斑

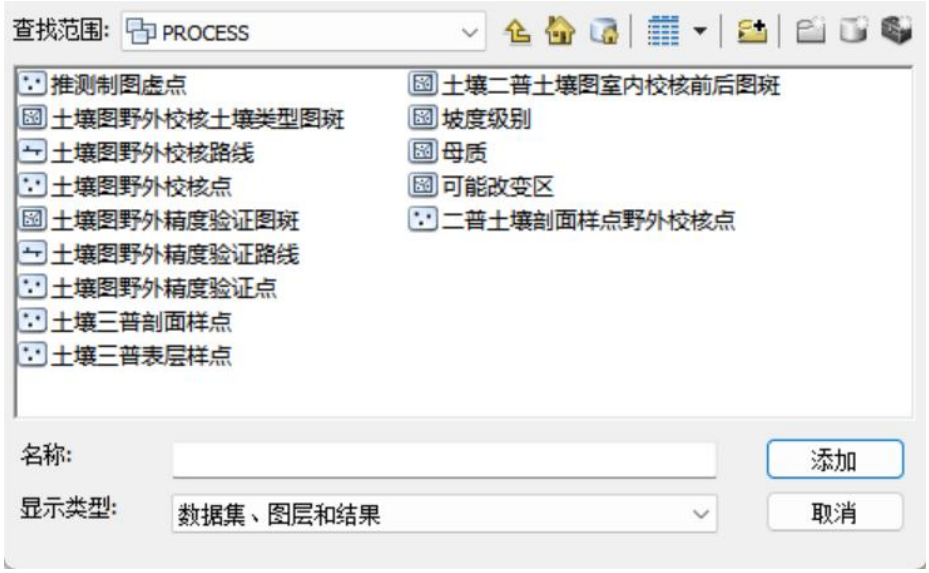


# 第七部分 质控意见

| | | | |
|---|---|---|---|
| **质控意见** | 整改后通过 | **质控日期** | 2026 年 6 月 7 日 |