内丘县耕地质量等级评价质控反馈
数据、图件和文字成果

一、图件成果 （没改）

1. 所有图例的文字和颜色要按照规范上的要求进行调整。①图例（河流图例不对、居民点文字描述不对，应该是居民地）。②地图投影坐标系标注不规范，应该采用高斯一克吕格投影（3°分带或6°分带）,请写完整。③编制单位应该注于图廓外左下方。

2.《规范》主要内容

要素类别	要素名称	图式符号	样式颜色
行政区名称	国家级行政区	中华人民共和国	K60，隶书
	省级行政区	江苏省 江苏省	M50Y50，隶书 K60，隶书（外围省）
	地级行政区	北京市 南京市 南京市	M50Y50，黑体（首都） K100，黑体 K60，黑体（外围地市）
	县级行政区	溧水区 溧水区	K100，楷体 K60，楷体（外围县）
	乡镇行政区	白马镇 白马镇	K100，仿宋体 K60，仿宋体（外围乡镇）
	村行政区	白马村 白马村	K100，宋体 K60，宋体（外围村）
主要城市驻地	首都	★ ★	M100Y100 K60（外围首都）
	省级政府驻地	◎ ◎	K100 K60（外围省）
	地级政府驻地	⊙ ⊙	K100 K60（外围地市）
	县级政府驻地	◎ ◎	K100 K60（外围县）
	乡镇政府驻地	⊙ ⊙	K100 K60（外围乡镇）
	村	○ ○	K100 K60（外围村）
	居民地		C33 M71 Y65 面色 M35 Y50
江河湖海	主要河流	长江	C100 C100K30，斜宋体
	主要湖泊	太湖	C20 C100 C100K30，斜宋体
	海洋	东海	C100M50 C100K30，斜宋体
主要交通设施	铁路		K60
	省道及以上公路		C41M100Y73

注记

图件主要注记省（区、区）、市（地、州、盟）、县（区、旗）、乡（镇、街道）政府驻地名称、重要河流、湖泊、水库名称及重要铁路、公路等，字体及颜色按规定设置，字体大小可根据幅面及区域大小进行调整。

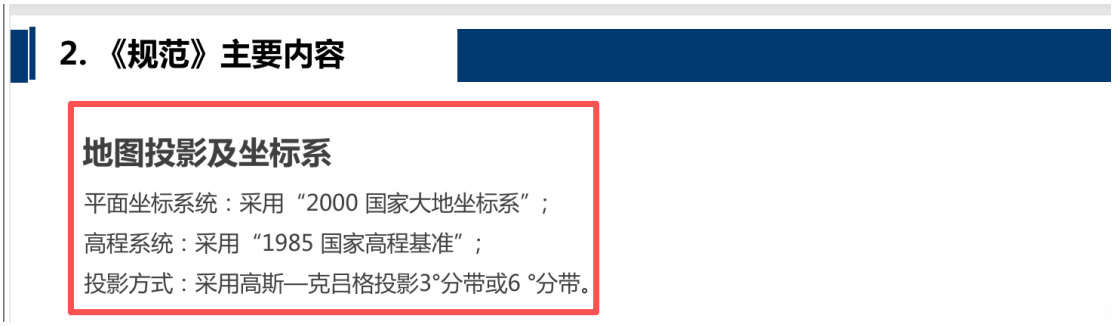

2.《规范》主要内容

地图投影及坐标系

平面坐标系统：采用“2000 国家大地坐标系”；

高程系统：采用“1985 国家高程基准”；

投影方式：采用高斯—克吕格投影3°分带或6 °分带。

2.《规范》主要内容

署名

图件应署编制单位的正式名称和制图日期，编制单位注于图廓外左下方，制图单位、日期注于图廓外右下方，字体为宋体。

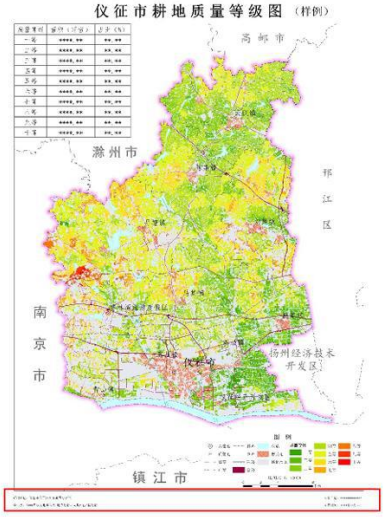

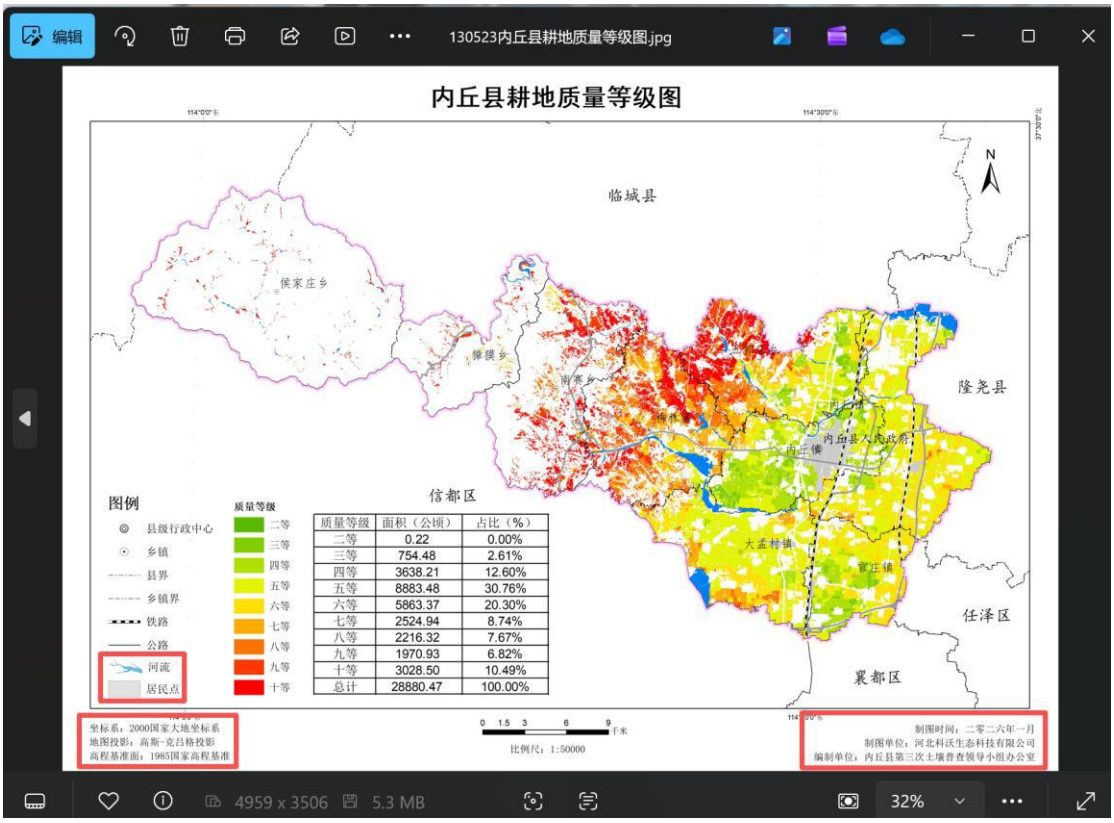

质量等级	面积（公顷）	占比（%）
二等	0.22	0.00%
三等	754.48	2.61%
四等	3638.21	12.60%
五等	8883.48	30.76%
六等	5863.37	20.30%
七等	2524.94	8.74%
八等	2216.32	7.67%
九等	1970.93	6.82%
十等	3028.50	10.49%
总计	28880.47	100.00%

2. 所有指标图件，缺少汇总表格。

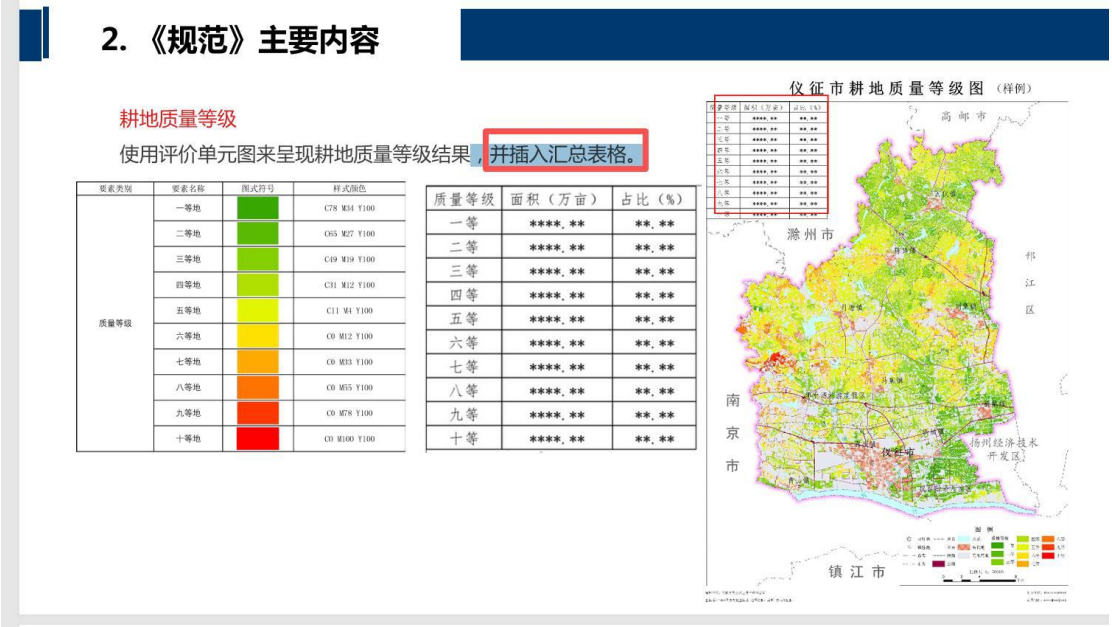

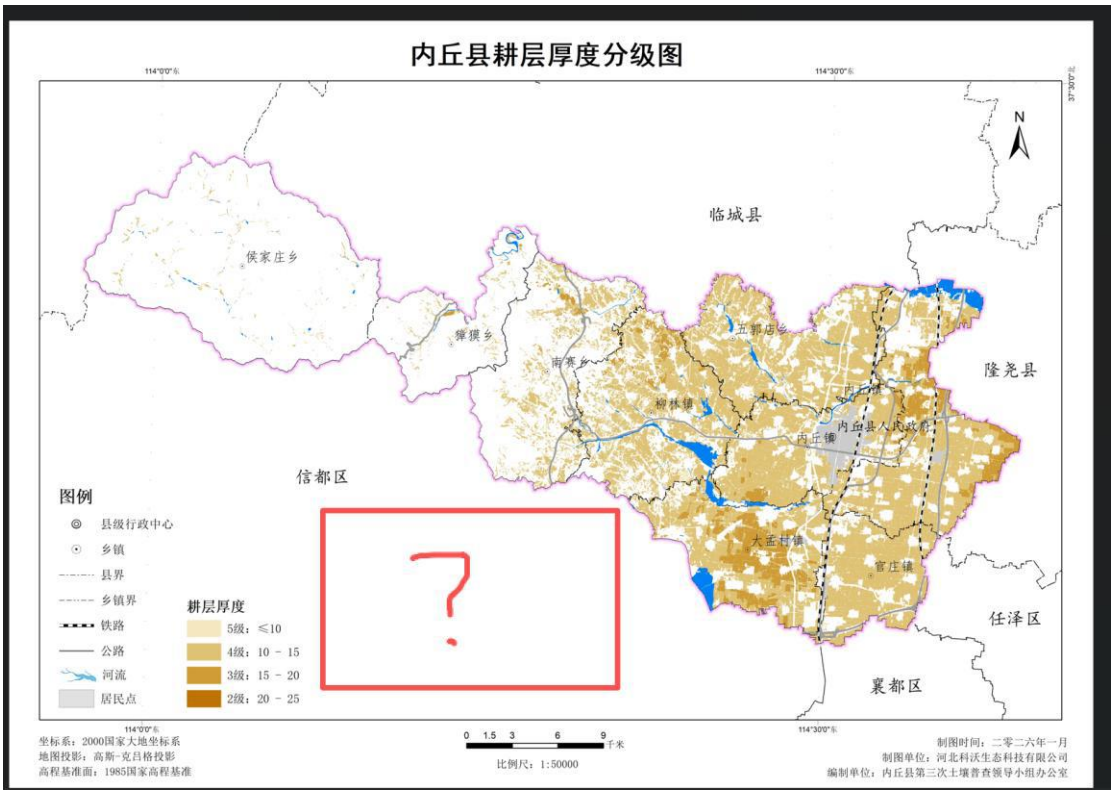

二、数据成果

无

三、文字成果

河北省第三次全国土壤普查

耕地质量等级评价文字问题整改复核报告

被检单位	河北科沃生态科技有限公司	区县/市名	内丘县
质控结果	整改复核：已修改且合规 2 项，已修改但不合规 3 项，未修改 0 项	质控日期	2026 年 9 月 8 日

复核依据与状态说明

上一批质控意见：耕地质量评价成果质控意见邢台市_130523 内丘县质控.pdf

本次文字报告：130523 内丘县耕地质量等级评价报告.docx

状态含义：“已修改且合规”表示相关内容已改且符合所列正式依据；“已修改但不合规”表示有改动但仍未达到正式要求；“未修改”表示现行文字报告中原问题仍存在且对应内容未作修改。

生产潜力

序号	上一批文字问题及正式依据	整改复核结果	本次核查位置及说明
1	耕地质量等级状况缺少对耕地质量分布的描述。①文字部分缺少 结合气候特点、地形地貌、母岩母质等简要阐述高、中、低等级耕地 总体分布情况与产能状况 （年产能和单季产能）的描述。②表 3.1 耕 地质量等级总体状况表格缺少年产量。 上一批位置：耕地质量评价成果质控意见邢台市_130523 内丘县质控.pdf，PDF 第 4 页 正式依据：《第三次全国土壤普查耕地质量等级评价技术规范》第 4.10.1—4.10.3 节	☐ 已修改且合规 ☑ 已修改但不合规 ☐ 未修改	现行报告耕地质量等级总体状况部分仍未完整结合气候、地形地貌和母岩母质说明高、中、低等级耕地分布及年度、单季产能状况，原问题未完全整改。

问题截图及备注

<table>
<tr><th>序号</th><th>问题截图</th><th>备注</th></tr>
<tr><td>1</td><td>上一批问题原件：《耕地质量评价成果质控意见邢台市_130523 内丘县质控.pdf》，PDF 第 4 页

1、耕地质量等级状况缺少对耕地质量分布的描述。①文字部分缺少结合气候特点、地形地貌、母岩母质等简要阐述高、中、低等级耕地总体分布情况与产能状况（年产能和单季产能）的描述。②表 3.1 耕地质量等级总体状况表格缺少年产量。

3.2 报告提纲
二、评价结果与分析
（一）耕地质量等级状况
重点介绍县（市、区、旗）耕地质量平均等级、面积、分布等。提供评价结果图（A3彩色折页）。
1. 耕地质量等级总体状况
提供本县（市、区、旗）耕地质量平均等级，文字部分不要简单重复表格已呈现信息，要结合气候特点、地形地貌、母岩母质等简要阐述高、中、低等级耕地总体分布情况与产能状况（年产能和单季产能）。
耕地质量等级总体状况（参考示例）
<table><tr><th>分级</th><th>面积/亩</th><th>比例/%</th><th>等级</th><th>面积/亩</th><th>比例/%</th><th>年产能（kg/亩）</th></tr><tr><td rowspan="3">高等级耕地</td><td rowspan="3"></td><td rowspan="3"></td><td>一等</td><td></td><td></td><td></td></tr><tr><td>二等</td><td></td><td></td><td></td></tr><tr><td>三等</td><td></td><td></td><td></td></tr><tr><td rowspan="3">中等级耕地</td><td rowspan="3"></td><td rowspan="3"></td><td>四等</td><td></td><td></td><td></td></tr><tr><td>五等</td><td></td><td></td><td></td></tr><tr><td>六等</td><td></td><td></td><td></td></tr><tr><td rowspan="4">低等级耕地</td><td rowspan="4"></td><td rowspan="4"></td><td>七等</td><td></td><td></td><td></td></tr><tr><td>八等</td><td></td><td></td><td></td></tr><tr><td>九等</td><td></td><td></td><td></td></tr><tr><td>十等</td><td></td><td></td><td></td></tr><tr><td colspan="7">总计</td></tr></table></td><td>R01：已修改但不合规。现行报告耕地质量等级总体状况部分仍未完整结合气候、地形地貌和母岩母质说明高、中、低等级耕地分布及年度、单季产能状况，原问题未完全整改。</td></tr>
</table>

序号	问题截图	备注
	本次现行文字报告复核位置：《130523 内丘县耕地质量等级评价报告.docx》，PDF 第 26 页 二、评价结果与分析 （一）耕地质量等级状况 1、耕地质量等级总体状况 耕地质量等级评价耕地面积为 433207 亩。评价结果为高等级耕地面积为 817 亩，占耕地总面积的 0.19%，细分地块中，三等地面积 817 亩，占比 0.19%；评价结果为中等级耕地面积为 285420 亩，占耕地总面积的 65.89%，细分地块中，四等地面积 82015 亩，占比 18.93%，五等地面积 115105 亩，占比 26.57%，六等地面积 94755 亩，占比 21.87%；评价结果为低等级耕地面积为 140515 亩，占耕地总面积的 32.44%，细分地块中，七等地面积 26434 亩，占比 6.10%，八等地面积 34585 亩，占比 7.98%，九等地面积 34285 亩，占比 7.91%，十等地面积 45211 亩，占比 10.44%。 表 3.1 耕地质量等级总体状况 分级 | 面积（亩） | 占比（%） | 质量等级 | 面积（亩） | 占比（%） 高等级耕地 | 817 | 0.19 | 三等地 | 817 | 0.19 中等级耕地 | 285420 | 65.89 | 四等地 | 82015 | 18.93 五等地 | 115105 | 26.57 六等地 | 94755 | 21.87 低等级耕地 | 140515 | 32.44 | 七等地 | 26434 | 6.10 八等地 | 34585 | 7.98 九等地 | 34285 | 7.91 十等地 | 45211 | 10.44 合计 | 433207 | 100 | — | — 2、各乡镇耕地质量状况	

指标插图与空间分析

序号	上一批文字问题及正式依据	整改复核结果	本次核查位置及说明
2	文本中缺少各指标因子的插图以及其空间分布特征的描述。 上一批位置：耕地质量评价成果质控意见邢台市_130523 内丘县质控.pdf，PDF 第 5 页 正式依据：《第三次全国土壤普查耕地质量等级评价工作方案》附件 2 一（四）（PDF 第 16 页）	☑ 已修改且合规 ☐ 已修改但不合规 ☐ 未修改	现行报告已逐指标说明基础数据来源，配置指标插图并说明空间分布特征，原问题已整改。

问题截图及备注

<table>
<tr><th>序号</th><th>问题截图</th><th>备注</th></tr>
<tr><td>2</td><td>
上一批问题原件：《耕地质量评价成果质控意见邢台市_130523 内丘县质控.pdf》，PDF 第 5 页

<table>
<tr><td>低等级耕地</td><td>9740.69</td><td>33.73</td><td>九等地</td><td>1970.93</td><td>6.82</td></tr>
<tr><td></td><td></td><td></td><td>十等地</td><td>3028.50</td><td>10.49</td></tr>
<tr><td>合计</td><td>28880.47</td><td>100</td><td>—</td><td></td><td></td></tr>
</table>

2、文本中缺少各指标因子的插图以及其空间分布特征的描述。


3.2 报告提纲

帽段：本县（市、区、旗）耕地面积、分布、所属耕地类型区的（到二级区）、包含的土壤类型、耕地质量基本状况等，评价目的意义等。

一、评价方法

（一）技术路线

（二）资料收集与整理

（三）评价单元划分

评价单元底图来源和比例尺、评价单元制作方法、评价单元数量等。

（四）评价指标体系建立

评价指标集、指标权重、指标隶属函数、综合指数计算与等级划分方法（结合实际详细阐述）；指标基础数据来源（分指标说明，包括比例尺或分辨率）、空间制图和评价单元赋值方法，提供各指标插图并简要分析其空间分布特征。

（五）评价结果验证

可使用产量验证法、对比验证法、专家验证法、实地验证法等。

（六）产能计算方法

本次现行文字报告复核位置：《130523 内丘县耕地质量等级评价报告.docx》，PDF 第 11 页

排水能力按照专家经验以及结合本地情况与农业生产经验，使用水利设施数据、坡度分级和三普调查数据，再叠加高标准农田数据进一步修正，最终实现排水能力的综合赋值。

8、指标空间分布特征

（1）地形部位

所有地形部位的耕地合计总面积 433207 亩，其中平原高阶耕地面积最大，达 191943 亩，占比 44.31%；平原低阶耕地面积 97969 亩，占比 22.61%，两者合计占比超 6 成；丘陵上部、丘陵下部、丘陵中部、山地坡上、山地坡下、山地坡中耕地面积分别为 19309、46496、71406、577、1375、4132 亩，占比依次为 4.46%、10.73%、16.48%、0.13%、0.32%、0.95%，整体耕地分布以平原低阶和高阶为主。

表 2.8 地形部位汇总表

地形部位	面积(亩)	占比（%）
平原低阶	97969	22.61
平原高阶	191943	44.31
丘陵上部	19309	4.46
丘陵下部	46496	10.73
丘陵中部	71406	16.48
山地坡上	577	0.13
山地坡下	1375	0.32
山地坡中	4132	0.95
总计	433207	100.00
</td><td>R02：已修改且合规。现行报告已逐指标说明基础数据来源，配置指标插图并说明空间分布特征，原问题已整改。</td></tr>
</table>

乡镇分析

序号	上一批文字问题及正式依据	整改复核结果	本次核查位置及说明
3	各乡镇耕地质量状况缺乏对主要限制因素的详细阐述。 上一批位置：耕地质量评价成果质控意见邢台市_130523 内丘县质控.pdf，PDF 第 6 页 正式依据：《第三次全国土壤普查耕地质量等级评价工作方案》附件 2 二（一）2 及表 2（PDF 第 18 页）	☐ 已修改且合规 ☑ 已修改但不合规 ☐ 未修改	现行报告已列出各乡镇等级面积及占比，但未逐乡镇说明主要限制因素，原问题未完全整改。

问题截图及备注

<table>
<tr><th>序号</th><th>问题截图</th><th>备注</th></tr>
<tr><td>3</td><td>
上一批问题原件：《耕地质量评价成果质控意见邢台市_130523 内丘县质控.pdf》，PDF 第 6 页

松散型	1324.73	4.59
海绵型	22256.85	77.07
薄层型	2883.43	9.98
合计	28880.47	100

3、各乡镇耕地质量状况缺乏对主要限制因素的详细阐述。

3.2 报告提纲

2. 各乡镇耕地质量状况

各乡镇耕地质量等级、面积、主要限制因素等（详细阐述），制作表格。

各乡镇耕地质量等级情况（参考示例）

乡镇	高等级耕地		中等等级耕地		低等等级耕地		合计
	面积(亩)	占比（%）	面积(亩)	占比（%）	面积(亩)	占比（%）	
乡镇1							
乡镇2							
……							
合计							

本次现行文字报告复核位置：《130523 内丘县耕地质量等级评价报告.docx》，PDF 第 26 页

			九等地	34285	7.91
			十等地	45211	10.44
合计	433207	100	—	—	

2、各乡镇耕地质量状况

高等级耕地方面，五郭店乡分布相对突出，面积达 603 亩，占高等级耕地总占比 0.14%；其次是内丘镇，面积为 161 亩，占比 0.04%；大孟村镇面积 53 亩，占比 0.01%；官庄镇、侯家庄乡、金店镇、柳林镇、南赛乡、獐猴乡无高等级耕地分布。

中等级耕地分布较广，金店镇是分布最多的乡镇，面积 87738 亩，占中等级耕地总占比 20.25%；其次是大孟村镇、内丘镇、五郭店乡、官庄镇，面积分别为 61137、56571、33790、45930 亩，占比 14.11%、13.06%、7.80%、10.60%；柳林镇、南赛乡、獐猴乡也有一定量分布，面积分别为 5367、640、669 亩，占比 1.24%、0.15%、0.15%；侯家庄乡分布最少，面积 34 亩，占比 0.01%。

24
</td><td>R03：已修改但不合规。现行报告已列出各乡镇等级面积及占比，但未逐乡镇说明主要限制因素，原问题未完全整改。</td></tr>
</table>

各等级特征

序号	上一批文字问题及正式依据	整改复核结果	本次核查位置及说明
4	耕地质量等级特征，内丘县内无一等地，不需要再进行文字描述。 上一批位置：耕地质量评价成果质控意见邢台市_130523 内丘县质控.pdf，PDF 第 7 页 正式依据：《第三次全国土壤普查耕地质量等级评价工作方案》附件 2 二（二）（PDF 第 18 页）	☐ 已修改且合规 ☑ 已修改但不合规 ☐ 未修改	现行报告仍设置并分析本县评价结果中不存在的一等地和二等地，未按实际等级范围调整，原问题未整改。

问题截图及备注

<table>
<tr><th>序号</th><th>问题截图</th><th>备注</th></tr>
<tr><td>4</td><td>上一批问题原件：《耕地质量评价成果质控意见邢台市_130523 内丘县质控.pdf》，PDF 第 7 页
占比 8.46%、3.51%、1.38%、1.79%、2.03%；官庄镇低等级耕地面积极少，仅 5.80 公顷，占比 0.06%。详见下表。
4、耕地质量等级特征，内丘县内无一等地，不需要再进行文字描述。
本次现行文字报告复核位置：《130523 内丘县耕地质量等级评价报告.docx》，PDF 第 28 页
<table><tr><td>河湖库渠</td><td>—</td><td>—</td><td>2</td><td>0.00</td><td>—</td><td>—</td><td>2</td></tr><tr><td>总计</td><td>817</td><td>0.19</td><td>291875</td><td>67.38</td><td>140515</td><td>32.44</td><td>433207</td></tr></table>（二）耕地质量等级特征
1、一等地
内丘县内无一等地，建议增施有机肥、坚持秸秆还田，平衡施肥，持续提升土壤地力，提升耕地等级。
2、二等地
内丘县内无二等地，建议增施有机肥、坚持秸秆还田，平衡施肥，持续提升土壤地力，提升耕地等级。
3、三等地
三等耕地面积为 817 亩，占耕地总面积的 0.19%，主要分布在官庄镇、内丘镇、五郭店乡。质地构型：包含海绵型、上紧下松型，土壤结构疏松，通气透水性良好。地形部位：以平原低阶为主，地势平坦，便于机械化耕作和灌排管理。有效土层厚度平均 110.0cm，土体深厚，保水保肥能力强；耕层厚度</td><td>R04：已修改但不合规。现行报告仍设置并分析本县评价结果中不存在的一等地，未按实际等级范围调整，原问题未整改。</td></tr>
</table>

版式与文字

序号	上一批文字问题及正式依据	整改复核结果	本次核查位置及说明
5	耕地质量等级状况部分也需要提供评价结果图。 上一批位置：耕地质量评价成果质控意见邢台市_130523 内丘县质控.pdf，PDF 第 8 页 正式依据：《第三次全国土壤普查耕地质量等级评价工作方案》附件 2 一（四）、二（一）	☑ 已修改且合规 ☐ 已修改但不合规 ☐ 未修改	现行报告已补充并正确引用评价结果图，原问题已整改。

问题截图及备注

序号	问题截图	备注
5	上一批问题原件：《耕地质量评价成果质控意见邢台市_130523 内丘县质控.pdf》，PDF 第 8 页 量为 16.32mg/kg，速效钾平均含量为 135.41mg/kg。 5、耕地质量等级状况部分也需要提供评价结果图。 **3.2 报告提纲** **二、评价结果与分析** （一）耕地质量等级状况 重点介绍县（市、区、旗）耕地质量平均等级、面积、分布等。提供评价结果图（A3彩色折页）。 1. 耕地质量等级总体状况 提供本县（市、区、旗）耕地质量平均等级，文字部分不要简单重复表格已呈现信息，要结合气候特点、地形地貌、母岩母质等简要阐述高、中、低等级耕地总体分布情况与产能状况（年产能和单季产能）。 耕地质量等级总体状况（参考示例） 分级 | 面积/亩 | 比例/% | 等级 | 面积/亩 | 比例/% | 年产能（kg/亩） 高等级耕地 | | | 一等 | | | 二等 | | | 三等 | | | 中等级耕地 | | | 四等 | | | 五等 | | | 六等 | | | 低等级耕地 | | | 七等 | | | 八等 | | | 九等 | | | 十等 | | | 总计 | | |	R05：已修改且合规。现行报告已补充并正确引用评价结果图，原问题已整改。