威县耕地质量等级评价质控反馈
数据、图件和文字成果

一、图件成果

1. 指标因子图件缺少汇总表格，如下图所示。

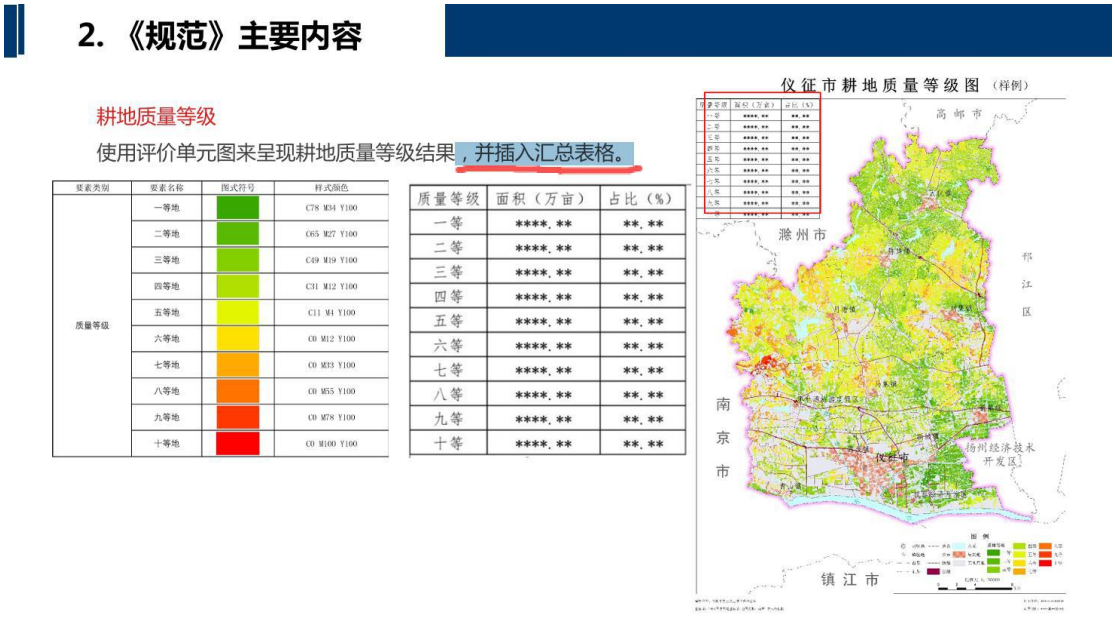

2. 《规范》主要内容

耕地质量等级

使用评价单元图来呈现耕地质量等级结果，并插入汇总表格。

要素类别	要素名称	图式符号	样式颜色
质量等级	一等地		C78 M34 Y100
	二等地		C65 M27 Y100
	三等地		C49 M19 Y100
	四等地		C31 M12 Y100
	五等地		C11 M4 Y100
	六等地		C0 M12 Y100
	七等地		C0 M33 Y100
	八等地		C0 M55 Y100
	九等地		C0 M78 Y100
	十等地		C0 M100 Y100

质量等级	面积（万亩）	占比（%）
一等	****.**	**.**
二等	****.**	**.**
三等	****.**	**.**
四等	****.**	**.**
五等	****.**	**.**
六等	****.**	**.**
七等	****.**	**.**
八等	****.**	**.**
九等	****.**	**.**
十等	****.**	**.**

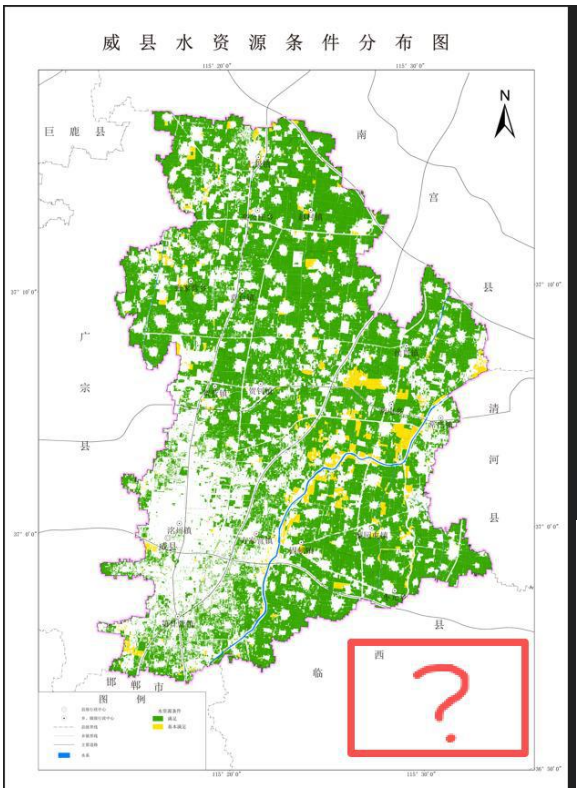

水资源条件	面积（万亩）	占比（%）
充分满足	6.34	18.27
满足	7.27	20.96
基本满足	12.54	36.15
不满足	8.55	24.63

2. 所有图件编制单位放在左下角

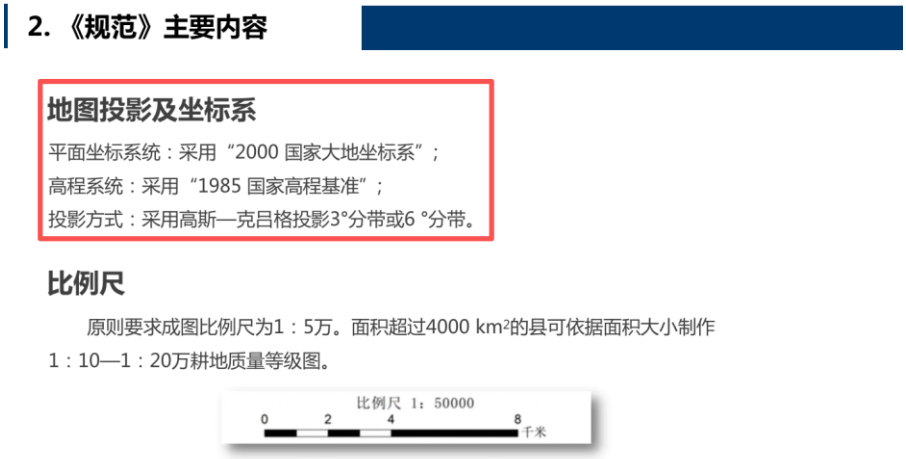



3、标题加粗

二、数据成果

无

三、文字成果

河北省第三次全国土壤普查

耕地质量等级评价文字问题整改复核报告

被检单位	河北诚秀科技有限公司	区县/市名	威县
质控结果	整改复核：已修改且合规 10 项，已修改但不合规 3 项，未修改 0 项	质控日期	2026 年 9 月 8 日

复核依据与状态说明

上一批质控意见：耕地质量评价成果质控意见_邢台市 130533 威县耕评质控.pdf

本次文字报告：威县耕地质量等级评价报告.docx

状态含义：“已修改且合规”表示相关内容已改且符合所列正式依据；“已修改但不合规”表示有改动但仍未达到正式要求；“未修改”表示现行文字报告中原问题仍存在且对应内容未作修改。

版式与文字

序号	上一批文字问题及正式依据	整改复核结果	本次核查位置及说明
1	目录，按照下面报告提纲的内容进行调整，请统一字体格式，全 部宋体不要加粗。 上一批位置：耕地质量评价成果质控意见_邢台市 130533 威县耕评质控.pdf，PDF 第 8 页 正式依据：《第三次全国土壤普查县级成果编制及验收导引》附录成果报告撰写格式要求	☐ 已修改且合规 ☑ 已修改但不合规 ☐ 未修改	现行报告目录仍未完全按规定提纲设置，目录字体未统一为宋体且仍有加粗，原问题未完全整改。

问题截图及备注

序号	问题截图	备注
1	上一批问题原件：《耕地质量评价成果质控意见_邢台市 130533 威县耕评质控.pdf》，PDF 第 8 页 **三、文字成果** 1、目录，按照下面报告提纲的内容进行调整，请统一字体格式，全部宋体不要加粗。 **3.2 报告提纲** 帽段：本县（市、区、旗）耕地面积、分布、所属耕地类型区的（到二级区）、包含的土壤类型、耕地质量基本状况等，评价目的意义等。 一、评价方法 （一）技术路线 （二）资料收集与整理 （三）评价单元划分 评价单元底图来源和比例尺、评价单元制作方法、评价单元数量等。 （四）评价指标体系建立 评价指标集、指标权重、指标隶属函数、综合指数计算与等级划分方法（结合实际详细阐述）；指标基础数据来源（分指标说明，包括比例尺或分辨率）、空间制图和评价单元赋值方法，提供各指标插图并简要分析其空间分布特征。 （五）评价结果验证 可使用产量验证法、对比验证法、专家验证法、实地验证法等。 （六）产能计算方法 **3.2 报告提纲** 二、评价结果与分析 （一）耕地质量等级状况 重点介绍县（市、区、旗）耕地质量平均等级、面积、分布等。提供评价结果图（A3彩色折页）。 1. 耕地质量等级总体状况 提供本县（市、区、旗）耕地质量平均等级，文字部分不要简单重复表格已呈现信息，要结合气候特点、地形地貌、母岩母质等简要阐述高、中、低等级耕地总体分布情况与产能状况（年产能和单季产能）。 耕地质量等级总体状况（参考示例） 分级 | 面积/亩 | 比例/% | 等级 | 面积/亩 | 比例/% | 年产能（kg/亩） 高等级耕地 | | | 一等 | | | | 二等 | | | | 三等 | | | | 四等 | | | | 本次现行文字报告复核位置：《威县耕地质量等级评价报告.docx》，PDF 第 3 页 2.指标权重 ..... 7 3.指标隶属度函数 ..... 7 4.综合指数计算 ..... 9 5.等级划分方法 ..... 9 6.指标基础数据来源 ..... 10 7.评价单元赋值方法 ..... 11 （五）评价结果验证 ..... 12 （六）耕地粮食生产潜力评估 ..... 16 1.某一评价单元耕地年度粮食生产潜力水平 ..... 16 2.某一评价单元耕地单季粮食产能水平 ..... 16 3.某一区域耕地年度粮食生产潜力 ..... 17 二、评价结果与分析 ..... 18 （一）耕地质量等级状况 ..... 18 1.耕地质量等级总体状况 ..... 21 2.各乡镇耕地质量状况 ..... 24 3.土壤类型耕地质量状况 ..... 28 （二）耕地质量等级特征 ..... 30 1.二等地 ..... 30 2.三等地 ..... 31 3.四等地 ..... 33 4.五等地 ..... 35 5.六等地 ..... 37 6.七等地 ..... 38 （三）各等级耕地主要属性对比 ..... 40 1.立地条件对比 ..... 40 2.理化性状对比 ..... 44 3.耕层养分对比 ..... 47 4.农田管理对比 52 5.粮食生产潜力水平对比 55	R01：已修改但不合规。现行报告目录仍未完全按规定提纲设置，目录字体未统一为宋体且仍有加粗，原问题未完全整改。

评价方法与基础数据

序号	上一批文字问题及正式依据	整改复核结果	本次核查位置及说明
2	技术路线，请参考规范中的技术路线，可以更全面，但是不可 以有遗漏。 上一批位置：耕地质量评价成果质控意见_邢台市 130533 威县耕评质控.pdf，PDF 第 9 页 正式依据：《第三次全国土壤普查耕地质量等级评价工作方案》附件 2 一（一）—（三）（PDF 第 16 页）	☑ 已修改且合规 ☐ 已修改但不合规 ☐ 未修改	现行报告已补充上一批指出的数据来源、评价单元或技术路线内容，原问题已整改。
3	①资料收集与整理请使用表格展示数据来源、年份、比例尺、格 式，请按照示例进行修改。②在耕地质量评价中并未使用的数据请不 要写在这里 （如高分影像等）， 这里的数据需要跟使用的数据一一对 应。 上一批位置：耕地质量评价成果质控意见_邢台市 130533 威县耕评质控.pdf，PDF 第 10 页 正式依据：《第三次全国土壤普查耕地质量等级评价工作方案》附件 2 一（一）—（三）（PDF 第 16 页）	☑ 已修改且合规 ☐ 已修改但不合规 ☐ 未修改	现行报告已补充上一批指出的数据来源、评价单元或技术路线内容，原问题已整改。
4	评价单元没有明确每个底图的来源（土地利用现状图、县域行政 区划图、土壤类型图来自哪儿？），并且缺少评价单元制作方法。 上一批位置：耕地质量评价成果质控意见_邢台市 130533 威县耕评质控.pdf，PDF 第 11 页 正式依据：《第三次全国土壤普查耕地质量等级评价工作方案》附件 2 一（一）—（三）（PDF 第 16 页）	☑ 已修改且合规 ☐ 已修改但不合规 ☐ 未修改	现行报告已补充上一批指出的数据来源、评价单元或技术路线内容，原问题已整改。

序号	上一批文字问题及正式依据	整改复核结果	本次核查位置及说明
5	①评价指标体系建立缺少对评价单元赋值方法的详细描述，请将 每个因子的赋值方法整理到一起。②缺少各指标插图以及其空间分 布特征的简要分析（请每个因子一个单独图+图名+对应的空间分布 特征文字描述）。③缺少耕地质量评价指标数据提取方法的文字描 述及表格展示，不可以进行截图（截图还是糊的）。 上一批位置：耕地质量评价成果质控意见_邢台市 130533 威县耕评质控.pdf，PDF 第 12 页 正式依据：《第三次全国土壤普查耕地质量等级评价工作方案》附件 2 一（一）—（三）（PDF 第 16 页）	☑ 已修改且合规 ☐ 已修改但不合规 ☐ 未修改	现行报告已补充上一批指出的数据来源、评价单元或技术路线内容，原问题已整改。
6	文本缺少评价指标权重确定、评价指标隶属度计算、综合指数计 算与等级划分方法。 上一批位置：耕地质量评价成果质控意见_邢台市 130533 威县耕评质控.pdf，PDF 第 15 页 正式依据：《第三次全国土壤普查耕地质量等级评价技术规范》第 4.6—4.8 节及附录 A、附录 B.3	☑ 已修改且合规 ☐ 已修改但不合规 ☐ 未修改	现行报告已补充评价指标、权重、隶属函数、综合指数及等级划分说明，原问题已整改。

问题截图及备注

<table>
<tr><th>序号</th><th>问题截图</th><th>备注</th></tr>
<tr><td>2</td><td>
上一批问题原件：《耕地质量评价成果质控意见_邢台市 130533 威县耕评质控.pdf》，PDF 第 9 页

2、 技术路线，请参考规范中的技术路线，可以更全面，但是不可以有遗漏。
本次现行文字报告复核位置：《威县耕地质量等级评价报告.docx》，PDF 第 4 页
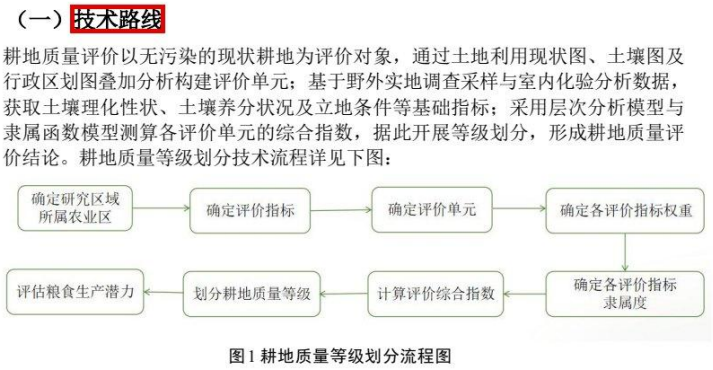

</td><td>R02：已修改且合规。现行报告已补充上一批指出的数据来源、评价单元或技术路线内容，原问题已整改。</td></tr>
<tr><td>3</td><td>
上一批问题原件：《耕地质量评价成果质控意见_邢台市 130533 威县耕评质控.pdf》，PDF 第 10 页

4、①资料收集与整理请使用表格展示数据来源、年份、比例尺、格式，请按照示例进行修改。②在耕地质量评价中并未使用的数据请不要写在这里（如高分影像等），这里的数据需要跟使用的数据一一对应。
</td><td>R04：已修改且合规。现行报告已补充上一批指出的数据来源、评价单元或技术路线内容，原问题已整改。</td></tr>
</table>

<table>
<tr><th>序号</th><th>问题截图</th><th>备注</th></tr>
<tr><td></td><td>本次现行文字报告复核位置：《威县耕地质量等级评价报告.docx》，PDF 第 4 页

图 1 耕地质量等级划分流程图
（二）资料收集与整理
威县位于冀鲁豫低洼平原农业区，根据《第三次全国土壤普查耕地质量等级评价技术规范》（国土壤普查办发〔2025〕9 号）相关要求，需要从立地条件、理化性状、耕层养分状况和农田管理方面收集水资源条件、有效土层厚度、有机质、耕层质地、排水能力、地形部位、耕层厚度、质地构型、有效磷、速效钾、土壤容重、盐渍化程度等数据来进行威县耕地质量评价，同时涉及制图等相关工作，具体的源数据收集如表 1。
表 1 数据来源表
<table><tr><th>名称</th><th>数据描述</th><th>来源</th></tr><tr><td>基础地理数据</td><td>行政区、居民点、道路、水系、土地利用类型图等</td><td>国家 1:100万基础地理信息数据库；国土三调数据</td></tr><tr><td>地形</td><td>主要获取地形部位等信息</td><td>SRTM 30m DEM，来源于 PIE-Engine 云平台、国土三调数据</td></tr><tr><td>三普土壤图</td><td>主要获取剖面性状</td><td>威县第三次土壤普查成果</td></tr><tr><td>三普表层外业调查数据</td><td>主要获取水资源条件、排水能力等</td><td>威县第三次土壤普查成果</td></tr><tr><td></td><td>主要获取耕层质地</td><td></td></tr></table></td><td></td></tr>
<tr><td>4</td><td>上一批问题原件：《耕地质量评价成果质控意见_邢台市 130533 威县耕评质控.pdf》，PDF 第 11 页
<table><tr><td>基础地理数据</td><td>行政区、居民点、道路、水系等</td><td>国家：万基础地理信息数据库；国土三调数据</td></tr></table>5、评价单元没有明确每个底图的来源（土地利用现状图、县域行政区划图、土壤类型图来自哪儿？），并且缺少评价单元制作方法。</td><td>R05：已修改且合规。现行报告已补充上一批指出的数据来源、评价单元或技术路线内容，原问题已整改。</td></tr>
</table>

<table>
<tr><th>序号</th><th>问题截图</th><th>备注</th></tr>
<tr><td></td><td>本次现行文字报告复核位置：《威县耕地质量等级评价报告.docx》，PDF 第 4 页

一、评价方法概述
（一）技术路线
耕地质量评价以无污染的现状耕地为评价对象，通过土地利用现状图、土壤图及行政区划图叠加分析构建评价单元；基于野外实地调查采样与室内化验分析数据，获取土壤理化性状、土壤养分状况及立地条件等基础指标；采用层次分析模型与隶属函数模型测算各评价单元的综合指数，据此开展等级划分，形成耕地质量评价结论。耕地质量等级划分技术流程详见下图：
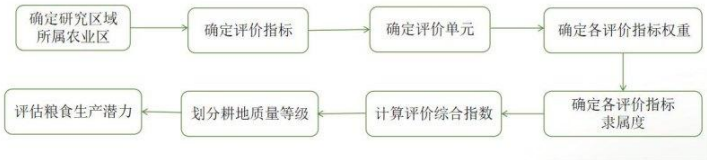

图 1 耕地质量等级划分流程图
（二）资料收集与整理
威县位于冀鲁豫低洼平原农业区，根据《第三次全国土壤普查耕地质量等级评价技术规范》（国土壤普查办发〔2025〕9 号）相关要求，需要从立地条件、理化性状、耕层养分状况和农田管理方面收集收集水资源条件、有效土层厚度、</td><td></td></tr>
<tr><td>5</td><td>大量图件数据比例尺1:10000-1:50000，栅格分辨率30m。
表7 冀鲁豫低洼平原农业区等级划分指数
<table>
<tr><th>数据名称</th><th>数据来源</th><th>赋值方法</th></tr>
<tr><td>地形部位</td><td>DEM数据、三普数据等</td><td>土壤属性数据提取</td></tr>
<tr><td>水资源条件</td><td>三普数据、降水数据、水利设施数据、高标准农田数据等</td><td>综合赋值</td></tr>
<tr><td>排水能力</td><td>三普数据、
高标准农田数据、水利设施等</td><td>综合赋值</td></tr>
<tr><td>耕层厚度、质地构型、有效土层厚度</td><td>三普数据、
土壤类型图成果、二普数据等</td><td>制作二普、三普土种数据关联获取</td></tr>
</table>
10</td><td>R06：评价指标体系建立已对评价单元赋值方法的详细描述。有耕地质量评价指标数据提取方法的文字描述及表格
展示</td></tr>
</table>

<table>
<tr><th>序号</th><th>问题截图</th><th>备注</th></tr>
<tr><td></td><td>
上一批问题原件：《耕地质量评价成果质控意见_邢台市 130533 威县耕评质控.pdf》，PDF 第 12 页

6、①评价指标体系建立缺少对评价单元赋值方法的详细描述，请将每个因子的赋值方法整理到一起。②缺少各指标插图以及其空间分布特征的简要分析（请每个因子一个单独图+图名+对应的空间分布特征文字描述）。③缺少耕地质量评价指标数据提取方法的文字描述及表格展示，不可以进行截图（截图还是糊的）。
本次现行文字报告复核位置：《威县耕地质量等级评价报告.docx》，PDF 第 11 页
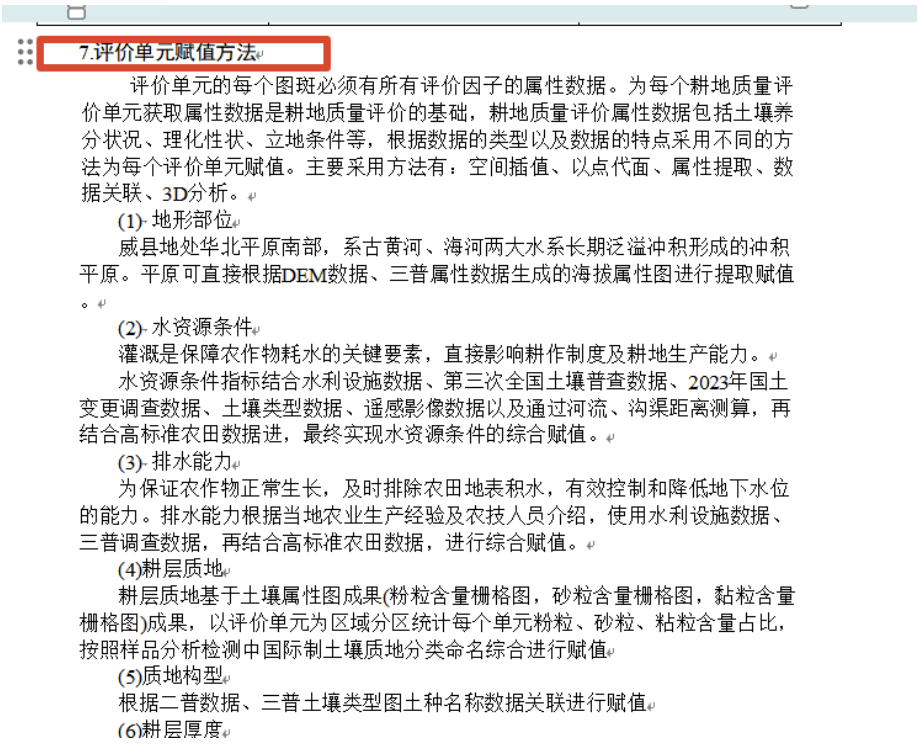
7.评价单元赋值方法
评价单元的每个图斑必须有所有评价因子的属性数据。为每个耕地质量评价单元获取属性数据是耕地质量评价的基础，耕地质量评价属性数据包括土壤养分状况、理化性状、立地条件等，根据数据的类型以及数据的特点采用不同的方法为每个评价单元赋值。主要采用方法有：空间插值、以点代面、属性提取、数据关联、3D分析。
(1)- 地形部位
威县地处华北平原南部，系古黄河、海河两大水系长期泛溢冲积形成的冲积平原。平原可直接根据DEM数据、三普属性数据生成的海拔属性图进行提取赋值。
(2)- 水资源条件
灌溉是保障农作物耗水的关键要素，直接影响耕作制度及耕地生产能力。
水资源条件指标结合水利设施数据、第三次全国土壤普查数据、2023年国土变更调查数据、土壤类型数据、遥感影像数据以及通过河流、沟渠距离测算，再结合高标准农田数据进，最终实现水资源条件的综合赋值。
(3)- 排水能力
为保证农作物正常生长，及时排除农田地表积水，有效控制和降低地下水位的能力。排水能力根据当地农业生产经验及农技人员介绍，使用水利设施数据、三普调查数据，再结合高标准农田数据，进行综合赋值。
(4)耕层质地
耕层质地基于土壤属性图成果(粉粒含量栅格图，砂粒含量栅格图，黏粒含量栅格图)成果，以评价单元为区域分区统计每个单元粉粒、砂粒、粘粒含量占比，按照样品分析检测中国际制土壤质地分类命名综合进行赋值
(5)质地构型
根据二普数据、三普土壤类型图土种名称数据关联进行赋值
(6)耕层厚度
</td><td></td></tr>
<tr><td>6</td><td></td><td>R08：已修改且合规。现行报告已补充评价指标、权重、隶属函数、综</td></tr>
</table>

序号	问题截图	备注
	上一批问题原件：《耕地质量评价成果质控意见_邢台市 130533 威县耕评质控.pdf》，PDF 第 15 页 间分布特征。 （五）评价结果验证 可使用产量验证法、对比验证法、专家验证法、实地验证法等。 （六）产能计算方法 8、文本缺少评价指标权重确定、评价指标隶属度计算、综合指数计算与等级划分方法。 （四）评价指标体系建立 1. 评价指标选取 2. 评价指标权重确定 3. 评价指标隶属度计算 4. 综合指数计算 5. 等级划分方法 6. 基础数据来源 7. 评价单元赋值方法 本次现行文字报告复核位置：《威县耕地质量等级评价报告.docx》，PDF 第 7 页 2. 指标权重 本次评价采用《耕地质量等级》中推荐的层次分析法结合特尔菲法来确定各评价指标的权重。层次分析法就是把复杂的问题按照它们之间的隶属关系排定一定的层次，再对每一层次进行相对重要性比较，最后得出它们之间的一种关系，从而确定它们各自的权重。根据《第三次全国土壤普查耕地质量等级评价技术规，威县适用于黄淮海区冀鲁豫低洼平原农业区的指标权重，具体见表。 表3 冀鲁豫低洼平原农业区指标权重表 冀鲁豫低洼平原农业区 指标名称 指标权重 水资源条件 0.153 耕层质地 0.145 质地构型 0.124 有机质 0.116 地形部位 0.086 盐渍化程度 0.085 排水能力 0.084 有效磷 0.063 速效钾 0.054 有效土层厚度 0.034 土壤容重 0.034 耕层厚度 0.022 3. 指标隶属度函数	合指数及等级划分说明，原问题已整改。

帽段与基本内容

序号	上一批文字问题及正式依据	整改复核结果	本次核查位置及说明
7	缺少冒段，帽段内容要简要，突出重点，要进行耕地质量平均等 级、土壤类型的描述。请参照下面示例进行修改。 上一批位置：耕地质量评价成果质控意见_邢台市 130533 威县耕评质控.pdf，PDF 第 10 页 正式依据：《第三次全国土壤普查耕地质量等级评价工作方案》附件 2 帽段（PDF 第 16 页）	☑ 已修改且合规 ☐ 已修改但不合规 ☐ 未修改	前言已补充帽段

问题截图及备注

序号	问题截图	备注
7	上一批问题原件：《耕地质量评价成果质控意见_邢台市130533威县耕评质控.pdf》，PDF第10页 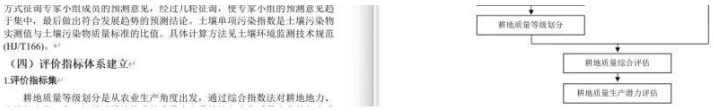 3、缺少冒段，帽段内容要简要，突出重点，要进行耕地质量平均等级、土壤类型的描述。请参照下面示例进行修改。 4、①资料收集与整理请使用表格展示数据来源、年份、比例尺、格式，请按照示例进行修改。②在耕地质量评价中并未使用的数据请不要写在这里（如高分影像等），这里的数据需要跟使用的数据一一对	R03：已修改

序号	问题截图	备注
	本次报告：《威县耕地质量等级评价报告.docx》，PDF 第 2 页，帽段 前言 威县耕地总面积 25076.70 公顷，有坝营镇、葛仙庄镇、连庄镇、王官庄镇、谢炉镇、油坊镇6个乡镇。从综合农业区划看，该县耕地隶属于黄淮海区的冀鲁豫低洼平原农业区，地势平坦、灌溉便利，光热资源充足，雨热同期，适宜小麦、玉米等粮食作物及棉花、蔬菜等经济作物生长。 土壤类型以潮土类为主，涵盖固定草甸风沙土、壤质石灰性潮土、壤质脱潮土、砂质石灰性潮土、砂质脱潮土等土属，其中壤质石灰性潮土面积最大，达 17497.76 公顷，是县域主要耕地土壤类型，其下均黏壤、均壤质、均砂壤等多种质地构成了区域耕地土壤的主体类型，土壤质地呈现“黏壤、壤质、砂质、砂壤质多元并存”的特征，受土壤质地、构型、水资源条件及人为管理等因素影响，威县耕地质量等级分化明显，整体以高等级耕地（二、三等地）为绝对主体，集中于优质土种与核心乡镇；中等级耕地（四、五、六等地）多分布于西部乡镇；低等级耕地（七等地）主要聚集于砂质、砂壤质土壤分布区域，存在沙质化等短板。 耕地质量平均等级为4.64，是全县二等地耕地分布最集中的乡镇，而油坊镇、谢炉镇等乡镇则以中等级耕地为主。 本次耕地质量评价，不仅全面摸清了县域耕地资源的质量及空间分布特征，构建了“质量等级 - 理化性状 - 生产潜力”的关联体系，为精准管控耕地、退化治理及产能提升提供了科学依据；从意义来看，一方面，评价成果为因地制宜开展耕地质量建设、提升耕地综合生产能力、特色农产品产业发展提供科学依据；另一方面，为落实耕地保护和粮食安全责任制考核、补充耕地质量验收等提供支撑。同时，本次评价结合土壤三普数据，为后续耕地质量常态化监管、退化趋势预警及农业高质量发展提供了重要技术支撑，对推动区域农业现代化与乡村振兴具有重要现实意义。	

结果验证

序号	上一批文字问题及正式依据	整改复核结果	本次核查位置及说明
8	缺少评价结果验证以及产能计算方法章节。 上一批位置：耕地质量评价成果质控意见_邢台市 130533 威县耕评质控.pdf，PDF 第 15 页 正式依据：《第三次全国土壤普查耕地质量等级评价工作方案》正文二（五）、附件 2 一（五）	☑ 已修改且合规 ☐ 已修改但不合规 ☐ 未修改	现行报告已说明采用的验证方法，列出具体量化结果和对比表，原问题已整改。

问题截图及备注

序号	问题截图	备注
8	上一批问题原件：《耕地质量评价成果质控意见_邢台市 130533 威县耕评质控.pdf》，PDF 第 15 页 7、 缺少评价结果验证以及产能计算方法章节。 **1.《规范》主要内容** **1.4.12 评价结果验证** **一是产量验证。**将各等级耕地质量对应的农作物调查产量进行对比统计，通过产量差异判断评价结果是否合理。 **二是对比验证。**通过对比不同质量等级耕地的指标值差异分析评价结果是否符合实际。 **三是专家验证。**邀请熟悉县域农业生产与耕地基本情况的专家，会同参与评价的专业人员，共同对评价过程和评价结果进行系统验证。 **四是实地验证。**抽取一定比例地块进行实地调查，验证耕地质量高低与地形优劣、作物产量高低等情况的吻合程度。耕地粮食生产潜力评估结果要与地方农业统计年鉴结果进行比对验证。 **3.2 报告提纲** 帽段：本县（市、区、旗）耕地面积、分布、所属耕地类型区的（到二级区）、包含的土壤类型、耕地质量基本状况等，评价目的意义等。 **一、评价方法** （一）技术路线 （二）资料收集与整理 （三）评价单元划分 评价单元底图来源和比例尺、评价单元制作方法、评价单元数量等。 （四）评价指标体系建立 评价指标集、指标权重、指标隶属函数、综合指数计算与等级划分方法（结合实际详细阐述）；指标基础数据来源（分指标说明，包括比例尺或分辨率）、空间制图和评价单元赋值方法，提供各指标插图并简要分析其空 本次现行文字报告复核位置：《威县耕地质量等级评价报告.docx》，PDF 第 12 页 (12)盐渍化程度 基于盐碱地专项调查形成的盐碱地成果专题数据，以耕地质量评价单元为空间分区，逐一提取对应区域内盐渍化程度专项调查属性信息，通过数据匹配与关联赋值，得到该地区耕地评价单元盐渍化程度指标值。 **（五）评价结果验证** 本次耕地质量评级专项对比，全域锚定威县全域在册在册耕地全域底数闭环研判，同步对标威县2023年度常态化耕地质量等级年度备案评价成果、第三次全国土壤普查规范化耕地质量等级全域定级评价两套法定核心台账成果逐项校核拆解。全程严守自然资源、农业农村双线实测原始地块台账、外业核查底图、实验室理化检测原始数据刚性溯源，先对齐两轮评价法定边界、全域统计口径、基础底数台账三大前置核心前提，再分层拆解耕地全域底数、全域平均质量等级、梯度等级地块结构、全域空间落地布局四项核心量化指标变化实况，深度溯源两轮评价指标范式、外业采样标准、分级定级规则、底数校核口径四大核心差异根源。全流程无主观推演、无台账变通、无口径偏差，刚性保障对比研判全程客观合规、数据闭环可溯源、结论贴合县域耕地实际禀赋，精准厘清两轮评级数值浮动核心本质，科学界定耕地本底质量实况与评价范式优化的边界差异，为威县后续耕地分级管控、地力定向提升、分区改良管护、高标准农田精准布局提供合规可用、台账可溯的硬核技术支撑。 **一、两轮评级全域底数对齐及核心结果变化实况精准研判** 刚性对齐两轮评价全域行政边界、耕地认定国土法定口径、地块上图入库标准，全域核心基础台账数据精准闭环核验无偏差。威县2023年常态化耕地质量等	R07：已修改且合规。现行报告已说明采用的验证方法，列出具体量化结果和对比表，原问题已整改。

乡镇分析

序号	上一批文字问题及正式依据	整改复核结果	本次核查位置及说明
9	①缺少耕地质量等级状况章节。②各乡镇耕地质量状况不能只对 表格内容进行简单的重复，需要总结归纳，对 各乡镇耕地质量等级、 面积、主要限制因素等进行详细阐述。 上一批位置：耕地质量评价成果质控意见_邢台市 130533 威县耕评质控.pdf，PDF 第 16 页 正式依据：《第三次全国土壤普查耕地质量等级评价工作方案》附件 2 二（一）2 及表 2（PDF 第 18 页）	☐ 已修改且合规 ☑ 已修改但不合规 ☐ 未修改	现行报告已列出各乡镇等级面积及占比，但未逐乡镇说明主要限制因素，原问题未完全整改。

问题截图及备注

<table>
<tr><th>序号</th><th>问题截图</th><th>备注</th></tr>
<tr><td>9</td><td>
上一批问题原件：《耕地质量评价成果质控意见_邢台市 130533 威县耕评质控.pdf》，PDF 第 16 页

9、①缺少耕地质量等级状况章节。②各乡镇耕地质量状况不能只对表格内容进行简单的重复，需要总结归纳，对各乡镇耕地质量等级、面积、主要限制因素等进行详细阐述。

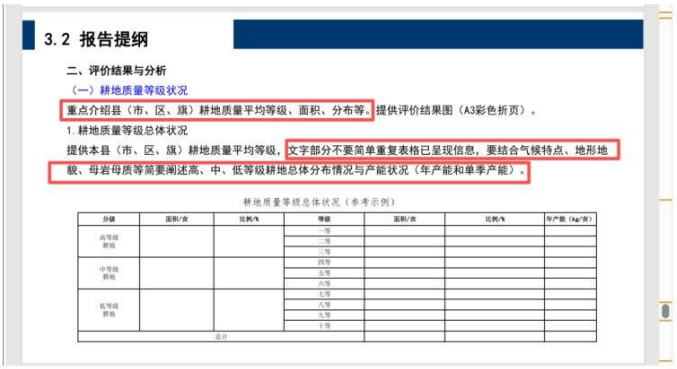
3.2 报告提纲

二、评价结果与分析

（一）耕地质量等级状况

重点介绍县（市、区、旗）耕地质量平均等级、面积、分布等。提供评价结果图（A3彩色折页）。

1. 耕地质量等级总体状况

提供本县（市、区、旗）耕地质量平均等级，文字部分不要简单重复表格已呈现信息，要结合气候特点、地形地貌、母岩母质等简要阐述高、中、低等级耕地总体分布情况与产能状况（年产能和单季产能）。

耕地质量等级总体状况（参考示例）

分级	面积/亩	比例/%	等级	面积/亩	比例/%	年产能（kg/亩）
高等级耕地			一等			
			二等			
			三等			
中等级耕地			四等			
			五等			
			六等			
低等级耕地			七等			
			八等			
			九等			
			十等			
总计						


3.2 报告提纲

2. 各乡镇耕地质量状况

各乡镇耕地质量等级、面积、主要限制因素等（详细阐述），制作表格。

各乡镇耕地质量等级情况（参考示例）

本次现行文字报告复核位置：《威县耕地质量等级评价报告.docx》，PDF 第 24 页

2.各乡镇耕地质量状况

常庄镇耕地总面积3039.63公顷，其中高等级耕地604.89公顷，占全县高等级耕地总量的2.64%；中等级耕地2417.74公顷，占全县中等级耕地总量的7.26%；低等级耕地17.00公顷，占全县低等级耕地总量的3.32%，耕地以中等地力为主体，零星搭配少量低等级短板地块。其耕地限制因素主要有：土壤养分上，全域耕地基础肥力整体中等，零星低等级耕地速效养分供给短板突出，局部中等级地块也存在肥力分层不均、后劲不足的实操问题；地形与土壤结构方面，全域无复杂地形起伏，耕作土层厚度达标、土体构型稳定，无深层结构性障碍短板，仅边缘零星地块轻度砂化扰动土质；灌溉排水上，田间主干灌排设施基础完备，但村组末梢支系管网衔接存在盲区，部分零散地块排灌联动效能偏低，直接制约局部地块产能稳定释放，是该镇常态化耕地提质管护的核心发力点。

第什营镇耕地总面积3318.05公顷，其中高等级耕地1192.19公顷，占全县高等级耕地总量的5.21%；中等级耕地2047.01公顷，占全县中等级耕地总量的6.14%；低等级耕地78.85公顷，占全县低等级耕地总量的15.41%，高、中、低三级耕地梯度配比均衡，全域耕地肌理错落分布。该乡镇耕地限制因素包括：土壤养分上，高等级耕地肥力禀赋优良、稳产性强，中低等级交叉
</td><td>R09：已修改但不合规。现行报告已列出各乡镇等级面积及占比，但未逐乡镇说明主要限制因素，原问题未完全整改。</td></tr>
</table>

各等级特征

序号	上一批文字问题及正式依据	整改复核结果	本次核查位置及说明
10	缺少耕地质量等级特征章节。 上一批位置：耕地质量评价成果质控意见_邢台市 130533 威县耕评质控.pdf，PDF 第 17 页 正式依据：《第三次全国土壤普查耕地质量等级评价工作方案》附件 2 二（二）（PDF 第 18 页）	☑ 已修改且合规 ☐ 已修改但不合规 ☐ 未修改	现行报告已设置分等级耕地质量特征章节，原问题已整改。
11	①各等级耕地主要属性对比请跟各个耕地质量等级进行比较分析， 提炼总结，请不要单纯的罗列表格中的数字。 上一批位置：耕地质量评价成果质控意见_邢台市 130533 威县耕评质控.pdf，PDF 第 18 页 正式依据：《第三次全国土壤普查耕地质量等级评价工作方案》附件 2 二（二）（PDF 第 18 页）	☑ 已修改且合规 ☐ 已修改但不合规 ☐ 未修改	现行报告已按不同等级比较主要属性并作归纳分析，原问题已整改。

问题截图及备注

序号	问题截图	备注
10	上一批问题原件：《耕地质量评价成果质控意见_邢台市 130533 威县耕评质控.pdf》，PDF 第 17 页 10、缺少耕地质量等级特征章节。 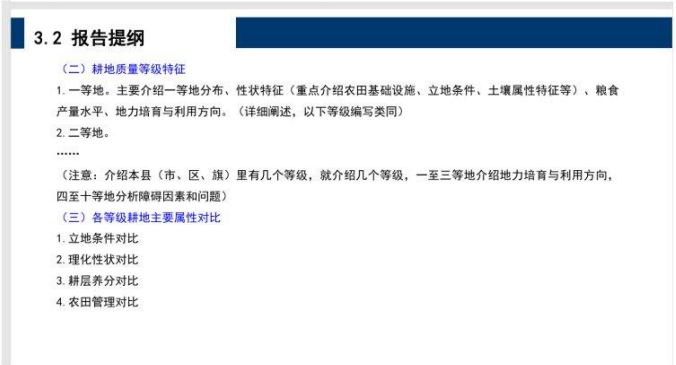 3.2 报告提纲 （二）耕地质量等级特征 1. 一等地。主要介绍一等地分布、性状特征（重点介绍农田基础设施、立地条件、土壤属性特征等）、粮食产量水平、地力培育与利用方向。（详细阐述，以下等级编写类同） 2. 二等地。 …… （注意：介绍本县（市、区、旗）里有几个等级，就介绍几个等级，一至三等地介绍地力培育与利用方向，四至十等地分析障碍因素和问题） （三）各等级耕地主要属性对比 1. 立地条件对比 2. 理化性状对比 3. 耕层养分对比 4. 农田管理对比 本次现行文字报告复核位置：《威县耕地质量等级评价报告.docx》，PDF 第 30 页 （二）耕地质量等级特征 1.二等地 二等地（总面积846.58公顷）为威县高等级耕地核心优质地块，全域呈点状规范布局、乡镇全覆盖无空白，整体地块规整度高、耕作基底优良，全面覆盖全县16个乡镇，空间布局均衡有序、无集中扎堆、无片区断层，完全契合威县平原全域耕地均质化连片基底禀赋特征。从乡镇台账量化占比梯度来看，枣元乡为全县二等地核心承载重点乡镇，二等地面积565.16公顷，占全县二等地总面积比重高达66.76%，体量优势遥遥领先，是县域二等优质良田绝对核心片区；常屯乡、七级镇、张家营乡为县域二等地重点配套片区，面积分别为48.02公顷、45.34公顷、42.43公顷，占比依次为5.67%、5.36%、5.01%，三片联动协同兜底优质耕地布局；贺营镇、贺钊镇、固献镇、侯贯镇、梨园屯镇、章台镇、洺州镇、第什营镇、方家营镇有序梯度配套分布，占比层级衔接顺畅；常庄镇、高公庄乡、赵村镇零星配套少量二等地地块，占比分别仅为0.22%、0.06%、0.16%，零散点缀全域田间肌理，全域无劣质空白乡镇、无连片短板片区，整体空间分布与县域水土资源、立地条件高度适配匹配。 一等耕地年度粮食生产潜力全域整体稳居高位水平，乡镇之间产能波动	R10：已修改且合规。现行报告已设置分等级耕地质量特征章节，原问题已整改。
11		R11：已修改且合规。现行报告已按不同等级比较主要属性并作归纳分

序号	问题截图	备注
	上一批问题原件：《耕地质量评价成果质控意见_邢台市 130533 威县耕评质控.pdf》，PDF 第 18 页 一等耕地所处地势平坦，是适应高产量要求的优质耕地，耕层较为疏，土体深厚，耕层厚度高，养地适中，通气适宜，保水保温性能解较好，是理想的农业土壤。增施有机肥和坚持秸秆还田，注意平衡施肥，以维护和继续提高土壤肥力。 3、一等地产能水平 将一等地评价综合指数得分代入产能拟合函数，计算每个图块的产能水平，整个耕地的产能水平为各个图块的产能水平加权面积数平均，评价结果显示一等耕地产能水平为值为1191 kg/亩。一等地产能水平高。 含量较高，部分地块存在酸化障碍，粮食平均产能水平为1196.96 kg/亩，今后应持续加强耕地保育和合理利用，推广测土配方施肥技术，消减酸化障碍。 从分布、属性特征、产能水平等方面描述。 11、①各等级耕地主要属性对比请跟各个耕地质量等级进行比较分析，提炼总结，请不要单纯的罗列表格中的数字。 示例 （二）理化性状对比 （三）各等级耕地主要属性对比 1、一等耕地质量特征 （1）立地条件 （2）土壤管理 （3）理化性质 各等级需要比较分析，不是分等级描述指标。 本次现行文字报告复核位置：《威县耕地质量等级评价报告.docx》，PDF 第 30 页 （二）耕地质量等级特征 1.二等地 二等地（总面积846.58公顷）为威县高等级耕地核心优质地块，全域呈点状规范布局、乡镇全覆盖无空白，整体地块规整度高、耕作基底优良，全面覆盖全县16个乡镇，空间布局均衡有序、无集中扎堆、无片区断层，完全契合威县平原全域耕地均质化连片基底禀赋特征。从乡镇台账量化占比梯度来看，枣元乡为全县二等地核心承载重点乡镇，二等地面积565.16公顷，占全县二等地总面积比重高达66.76%，体量优势遥遥领先，是县域二等优质良田绝对核心片区；常屯乡、七级镇、张家营乡为县域二等地重点配套片区，面积分别为48.02公顷、45.34公顷、42.43公顷，占比依次为5.67%、5.36%、5.01%，三片联动协同兜底优质耕地布局；贺营镇、贺钊镇、固献镇、侯贯镇、梨园屯镇、章台镇、洺州镇、第什营镇、方家营镇有序梯度配套分布，占比层级衔接顺畅；常庄镇、高公庄乡、赵村镇零星配套少量二等地地块，占比分别仅为0.22%、0.06%、0.16%，零散点缀全域田间肌理，全域无劣质空白乡镇、无连片短板片区，整体空间分布与县域水土资源、立地条件高度适配匹配。 一等耕地年度粮食生产潜力全域整体稳居高位水平，乡镇之间产能波动	析，原问题已整改。

统计与内部一致性

序号	上一批文字问题及正式依据	整改复核结果	本次核查位置及说明
12	不可以标题后直接接表格， 表格上面必须要有表名，先文字描述 后表格， 并且所有的关于面积统计的单位请使用公顷， 请全文进行统 一。 上一批位置：耕地质量评价成果质控意见_邢台市 130533 威县耕评质控.pdf，PDF 第 19 页 正式依据：《第三次全国土壤普查市县级成果验收工作方案》附件 3 表 3.5-5“结果分析”“报告质量”	☑ 已修改且合规 ☐ 已修改但不合规 ☐ 未修改	现行报告已在相关表格前补充文字说明和表名，面积统计统一使用公顷，原问题已整改。

问题截图及备注

<table>
<tr><th>序号</th><th>问题截图</th><th>备注</th></tr>
<tr><td>12</td><td>
上一批问题原件：《耕地质量评价成果质控意见_邢台市 130533 威县耕评质控.pdf》，PDF 第 19 页

12、不可以标题后直接接表格，表格上面必须要有表名，先文字描述后表格，并且所有的关于面积统计的单位请使用公顷，请全文进行统一。

99.39%，面积 743.22 亩；四级有机质占比仅 0.61%，面积 4.58 亩。

（2）有效磷

等级	属性	有效磷分级标准				
		一级	二级	三级	四级	五级
		>30	25.0-30.0	15.0-25.0	10.0-15.0	≤10.0
三等	面积/亩	15678.78	13251.45	40748.86	20554.86	8045.16
	占比/%	15.95	13.48	41.46	20.91	8.19
四等	面积/亩	42025.65	39567.90	164029.01	41627.39	6955.39
	占比/%	14.28	13.45	55.75	14.15	2.36
五等	面积/亩	7523.64	12713.89	154750.06	207563.11	58830.11
	占比/%	1.70	2.88	35.06	47.03	13.33
六等	面积/亩	343.53	403.02	7445.13	6514.99	3370.67
	占比/%	1.90	2.23	41.18	36.04	18.65
七等	面积/亩		1.26	334.15	31.03	381.35
	占比/%		0.17	44.69	4.15	51.00

从各等级耕地分布看，三等至七等地中，三等地一级有效磷占比 15.95%，二级占比 13.48%，三级占比 41.46%，四级占比 20.91%，五级占比 8.19%；四等地一级有效磷占比 14.28%，二级占比 13.45%，三级占比 55.75%，四级占比 14.15%，五级占比 2.36%；五等地一级有效磷占比 1.70%，二级占比 2.88%，三级占比 35.06%，四级占比 47.03%，五级占比 13.33%；六等地一级有效磷占比 1.90%，二级占比 2.23%，三级占比 41.18%，四级占比 36.04%，五级占比 18.65%；七等地无一级有效磷耕地，二级占比 0.17%，三级占比 44.69%，四级占比 4.15%，五级占比 51.00%。
</td><td>R12：已修改且合规。</td></tr>
</table>

序号	问题截图	备注
	本次现行文字报告复核位置：《威县耕地质量等级评价报告.docx》，PDF 第 48 页 七等 占比/% 69.04 30.96 0.00 （2）有效磷 从威县各等级耕地有效磷含量分布情况来看，全县耕地有效磷涵盖1级（>40mg/kg）、2级（30-40mg/kg）、3级（20-30mg/kg）、4级（10-20mg/kg）、5级（≤10mg/kg）五个分级，有效磷含量与耕地质量等级呈显著正相关，高等级耕地高含量有效磷占比更高，磷素养分储备充足；随着耕地等级逐步降低，高等级有效磷占比持续缩减，中低、低含量有效磷逐步占据绝对主导，耕层磷素贫瘠化特征不断凸显，梯度变化规律十分鲜明。 二等地有效磷完整覆盖全部五个分级区间，无5级（≤10mg/kg）极低含量磷素分布，整体以3级（20-30mg/kg）中等偏上有效磷为绝对主导，面积467.83公顷，占比55.26%；其次为4级（10-20mg/kg）中等含量有效磷，面积374.69公顷，占比44.26%；2级（30-40mg/kg）较高含量有效磷仅有少量分布，面积3.26公顷，占比0.39%；1级（>40mg/kg）高含量有效磷呈零星分布，面积0.80公顷，占比0.09%。整体来看，二等优质耕地无极低磷素贫瘠地块，中高含量有效磷配比充足，土壤供磷能力优良，磷素养分供应稳定，能够充分满足粮食作物生长周期内的磷素营养需求。 48 表18 不同土壤有效磷下质量等级各分级的耕地面积 等级 属性 有效磷分级标准（mg/kg） 1级 >40 2级 30-40 3级 20-30 4级 10-20 5级 ≤10 二等 面积/公顷 0.80 3.26 467.83 374.69 0.00 占比/% 0.09 0.39 55.26 44.26 0.00 三等 面积/公顷 3.27 152.84 4787.61 16248.19 845.02 占比/% 0.01 0.69 21.73 73.73 3.83 四等 面积/公顷 33.23 45.54 3037.76 19106.84 2736.48 占比/% 0.13 0.18 12.17 76.55 10.96 五等 面积/公顷 0.00 2.45 454.73 4909.84 972.88 占比/% 0.00 0.04 7.17 77.44 15.35 面积/公顷 0.00 1.05 205.44 1598.93 213.08	

问题、成因与对策

序号	上一批文字问题及正式依据	整改复核结果	本次核查位置及说明
13	针对存在的问题， 分区分类分别提出不同问题的解决对策与建议 （参照示例）。不要最后的对策建议和存在的问题根本对不上。 并且 请按照本县土壤存在的问题进行针对性的撰写。 上一批位置：耕地质量评价成果质控意见_邢台市 130533 威县耕评质控.pdf，PDF 第 20 页 正式依据：《第三次全国土壤普查耕地质量等级评价工作方案》附件 2 三（三）（PDF 第 19 页）	☑ 已修改且合规 ☐ 已修改但不合规 ☐ 未修改	现行报告已提出与问题和成因对应的对策措施，原问题已整改。

问题截图及备注

<table>
<tr><th>序号</th><th>问题截图</th><th>备注</th></tr>
<tr><td>13</td><td>

上一批问题原件：《耕地质量评价成果质控意见_邢台市 130533 威县耕评质控.pdf》，PDF 第 20 页

13、针对存在的问题，分区分类分别提出不同问题的解决对策与建议（参照示例）。不要最后的对策建议和存在的问题根本对不上。并且请按照本县土壤存在的问题进行针对性的撰写。

本次现行文字报告复核位置：《威县耕地质量等级评价报告.docx》，PDF 第 56 页

六等	面积/公顷	0.00	0.00	0.00	1028.13	990.38
	占比/%	0.00	0.00	0.00	50.94	0.00
七等	面积/公顷	0.00	0.00	0.00	0.00	511.67
	占比/%	0.00	0.00	0.00	0.00	0.00

三、存在问题及对策建议

（一）存在问题

1. 耕地质量等级空间分化显著，高低等级耕地布局差异突出

威县耕地质量等级空间分异特征明显，整体耕地质量呈现“中部优、局部弱”的分布格局，高低等级耕地片区化集聚特征突出。全县二、三等地作为优势耕地主体，广泛分布于坝营镇、连庄镇、油坊镇、谢炉镇等区域，耕地地力优良、产能稳定，是全县粮食高产稳产的核心承载区。相较优质片区，县域局部乡镇耕地质量短板问题突出，葛仙庄镇、王官庄镇中低等级耕地集中分布，低等级耕地连片集聚态势明显。其中葛仙庄镇五至七等地占比偏高，低质地、低肥力、低产能耕地集中连片，是全县耕地质量提升的重点攻坚区域；王官庄镇六、七等地呈零散分布状态，局部耕地质量短板突出，制约区域耕地整体产能提升。全县七等地面积511.67公顷，集中分布于低等级耕地短板片区，虽全域占比不高，但局部地块耕地产能薄弱、改良紧迫性极强，区域耕地质量不均衡问题突出。

2. 耕层质地劣化明显，砂质化成为低等级耕地核心障碍

全县耕地耕层质地随质量等级降低呈现显著的砂质化劣变规律，质地结构失衡是制约低等级耕地质量的核心物理障碍。高等级二、三等地以保水保肥性能

</td><td>R13：已修改且合规。现行报告已提出与问题和成因对应的对策措施，原问题已整改。</td></tr>
</table>